20 de novembro de 2012

Introduzidas precisões de texto nas páginas 11 e 26 (20 novembro, 17:00h)

Censos 2011

Momento Censitário – 21 de março 2011

XV recenseamento geral da população
CENSOS 2011
V recenseamento geral da habitação

População cresce 2% na última década graças ao saldo migratório

A população residente em Portugal, à data do momento censitário (21 de Março de 2011) era de 10 562 178 pessoas, das quais 5 046 600 são homens e 5 515 578 são mulheres, de acordo com os resultados definitivos dos Censos 2011.

Toda a informação sobre população, família e habitação, em síntese neste Destaque.

A população

O crescimento de 2% da população (206 061 pessoas) verificado nos últimos dez anos deveu-se predominantemente a um saldo migratório positivo de 188 652, uma vez que o saldo natural (número de nascimentos menos o número de óbitos) contribuiu com apenas 17 409 pessoas para este crescimento.

População residente em 2001 e 2011

Portugal	2001		2011	
	Nº	%	Nº	%
População residente	10 356 117	100	10 562 178	100
Homens	5 000 141	48,3	5 046 600	47,8
Mulheres	5 355 976	51,7	5 515 578	52,2

Onde reside a população

A Região do Alentejo voltou a perder população (cerca de 2,5%, ou seja 19 283 pessoas) face a 2001, bem como a Região Centro, cuja população recuou sensivelmente 1%. A Região Norte manteve praticamente a população que tinha na última década. Apresentaram saldo positivo a Região do Algarve (+14%), as RA dos Açores (+2%) e da Madeira (9%) e a Região de Lisboa (+6%).

www.ine.pt | Serviço de Comunicação e Imagem - Tel: +351 21.842.61.00 - sci@ine.pt

Variação da população residente por NUTS II entre 2001 e 2011

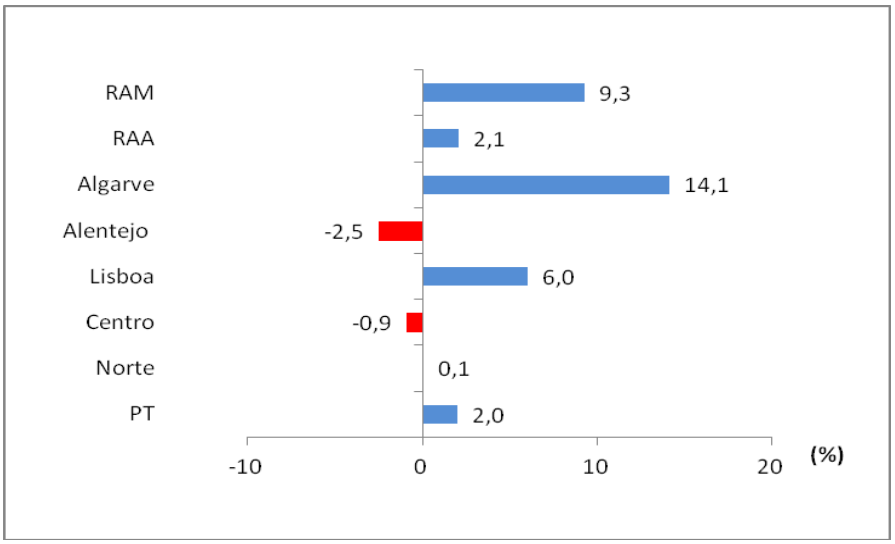

Mais de 80% da população residente concentrava-se em 3 regiões do país: Norte (34,9%), Lisboa (26,7%) e Centro (22,0%). A restante população distribui-se pelas regiões do Alentejo (7,2%), Algarve (4,3%), R.A. Madeira (2,5%) e R.A. Açores (2,3%).

População residente em Portugal, por NUTS II, em 2011

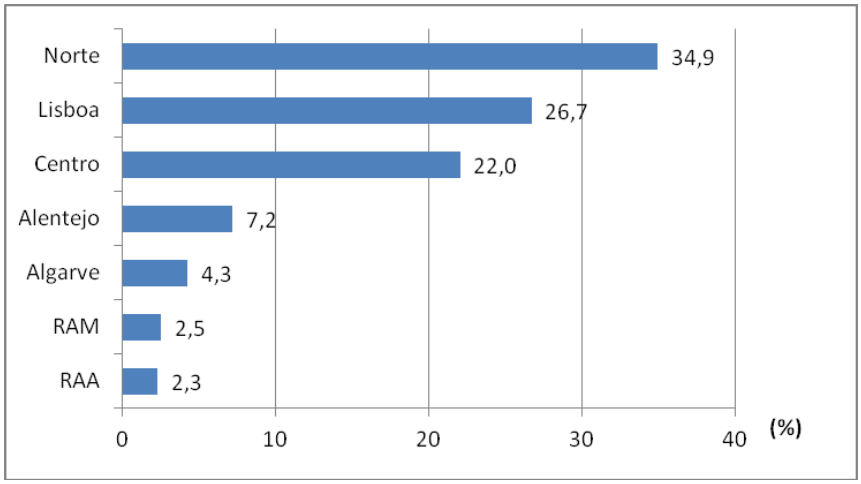

Desertificação no interior do país aumentou na última década; 50% da população residente concentra-se em 33 dos 308 municípios do país.

Na última década, continuou a assistir-se à perda de população nos municípios do interior e ao efeito de concentração da população nos municípios do litoral. De acordo com os resultados definitivos dos Censos 2011, cerca de 50% da população concentra-se em 33 municípios do país.

Na década terminada em 2001, 171 municípios tinham perdido população; já no que se refere à última década, o número de municípios cuja população decresceu subiu para 198.

Variação da população residente por município entre 2001 e 2011
Os 10 mais e os 10 menos

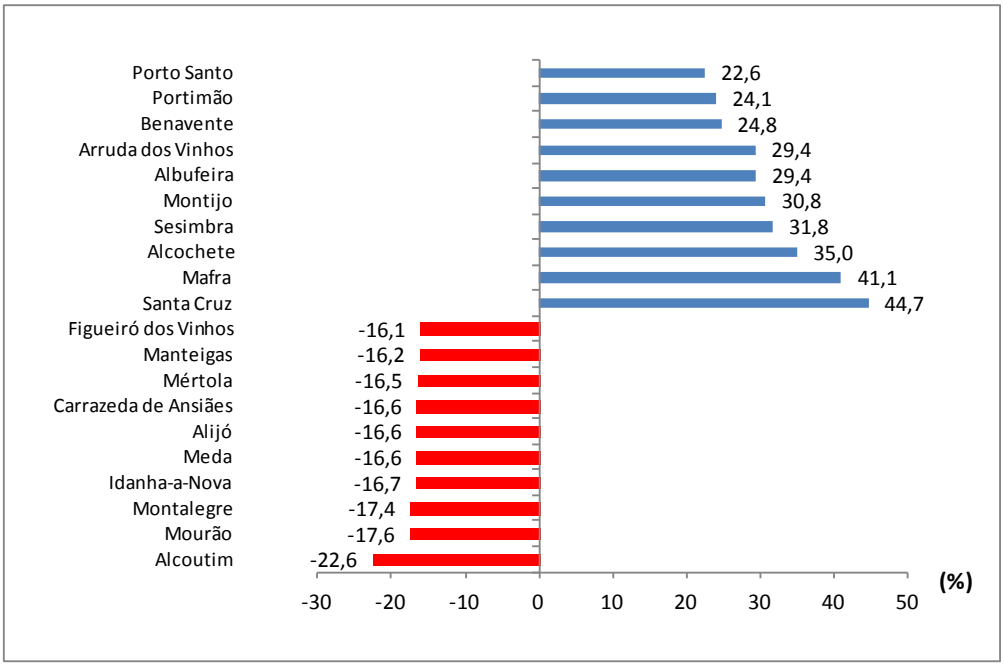

Os 10 Municípios que ganharam mais população

Com crescimentos acima dos 40%: Santa Cruz (44,7%) na RA da Madeira e Mafra (41,1%).

Com crescimentos entre 30% e 40%: Alcochete (35,0%), Sesimbra (31,8%) e Montijo (30,8%).

Com crescimentos entre 20% e 30%: Albufeira (29,4%), Arruda dos Vinhos (29,4%), Benavente (24,8%), Portimão (24,1%) e Porto Santo (22,6%).

Os 10 Municípios que perderam mais população

Com queda superior a 20%: Alcoutim com -22,6%.

Com quedas entre 10% e 20%: Mourão (-17,6%), Montalegre (-17,4%), Idanha-a-Nova (-16,7%), Meda (-16,6%), Alijo (-16,6%), Carrazeda de Ansiães (-16,6%), Mértola (-16,5%), Manteigas (-16,2%) e Figueiró dos Vinhos (-16,1%).

Dos 10 Municípios mais populosos do país, 6 localizam-se na Região de Lisboa e 4 na Região Norte

Em 2011, o grupo dos 10 municípios mais populosos alterou-se ligeiramente, em relação a 2001:

- Lisboa, Sintra, Vila Nova de Gaia e Porto mantiveram-se nas quatro primeiras posições
- O município de Gondomar deixou de integrar o grupo;
- Almada passou a integrar o grupo;
- Cascais reforçou a sua posição, tendo passado para 5º lugar, agora à frente de Loures e da Amadora;
- Braga ultrapassou Matosinhos.

Os 10 municípios com mais população residente em 2001 e 2011

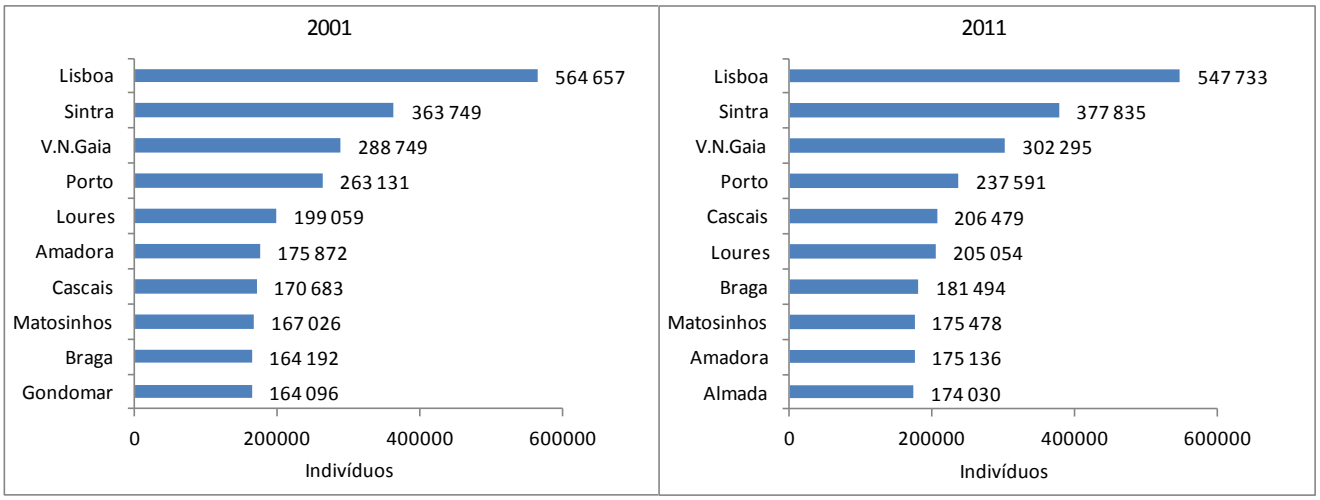

Na última década, 7 dos 10 municípios mais populosos ganharam população:

Cascais	+21% (35 796 pessoas),
Braga	+10,5% (17 302 pessoas),
Almada	+8,2% (13 205 pessoas),
Matosinhos	+5,1% (8 452 pessoas),
Vila Nova de Gaia	+4,7% (13 546 pessoas),
Sintra	+3,9% (14 086 pessoas),
Loures	+3% (5 995 pessoas).

Perderam população:

Porto	-9,7% (25 540 pessoas),
Lisboa	-3,0% (16 924 pessoas),
Amadora	-0,5% (736 pessoas).

Variação da população residente nos 10 municípios mais populosos entre 2001 e 2011

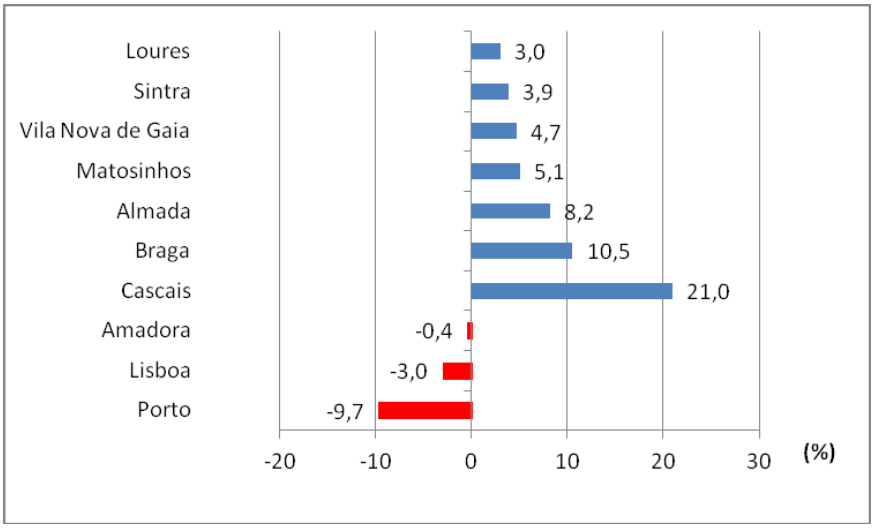

Indicadores demográficos

Percentagem de jovens recuou para 15% e de idosos cresceu para 19%

A estrutura etária da população acentuou os desequilíbrios já evidenciados na década passada. Diminuiu a base da pirâmide, correspondente à população mais jovem, e alargou-se o topo, com o crescimento da população mais idosa.

Estrutura etária da população residente, por sexo, 2001 e 2011

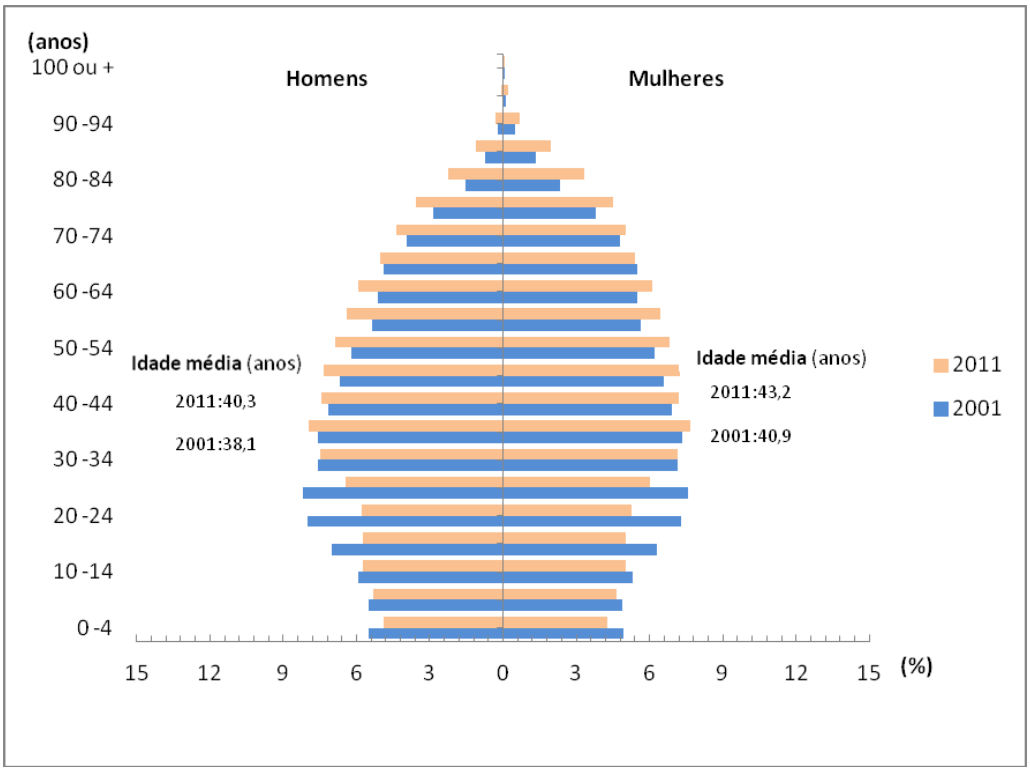

Portugal perdeu população em todos os grupos etários (de cinco anos) entre os 0-29 anos.

A população entre os 30 e os 69 anos cresceu 9% e, para idades superiores a 69 anos, o crescimento foi da ordem dos 26%.

Estrutura etária da população, 2001 e 2011

Portugal	2001		2011	
	Nº	%	Nº	%
Estrutura Etária				
0-14 anos	1 656 602	16,0	1 572 329	14,9
15-24 anos	1 479 587	14,3	1 147 315	10,9
25-64 anos	5 526 435	53,4	5 832 470	55,2
65 ou mais anos	1 693 493	16,4	2 010 064	19,0

Idade média da população aumentou 3 anos numa década: é agora de 41,8 anos

A idade média da população residente aumentou, na última década, cerca de 3 anos, tendo-se fixado nos 41,8 anos. A idade média das mulheres (43,2 anos) é superior à dos homens, (40,3 anos).

Idade média da população residente, por NUTS II, 2001 e 2011

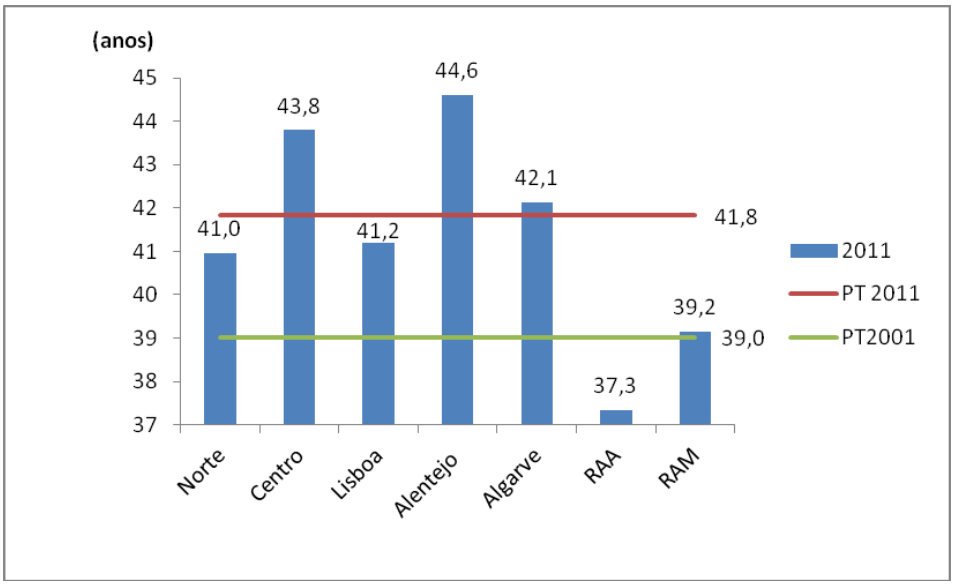

A idade média da população das Regiões Autónomas era bastante inferior à média nacional. Na situação oposta, encontrava-se a Região do Alentejo, cuja população apresentava a idade média mais elevada do país.

Os índices demográficos apurados apontam para o envelhecimento acelerado da população:

Indicadores demográficos	2001	2011
Índice de envelhecimento	102,23	127,84
Índice de longevidade	41,42	47,86
Índice de rejuvenescimento da população ativa	143,05	94,34
Índice de sustentabilidade potencial	4,14	3,47

Índice de envelhecimento

Em 2011, o índice de envelhecimento da população era de 128, o que significa que por cada 100 jovens existiam 128 idosos.

As Regiões Autónomas apresentavam os índices de envelhecimento mais baixos do país, respetivamente 73 para a R.A. dos Açores e 91 para a R.A. da Madeira. Estas eram as únicas regiões do país com mais jovens do que idosos.

No polo oposto encontravam-se as Regiões do Centro e Alentejo, como as regiões mais envelhecidas, com índices de 163 e 178 respetivamente.

Índice de envelhecimento, por NUTS II, 2001 e 2011

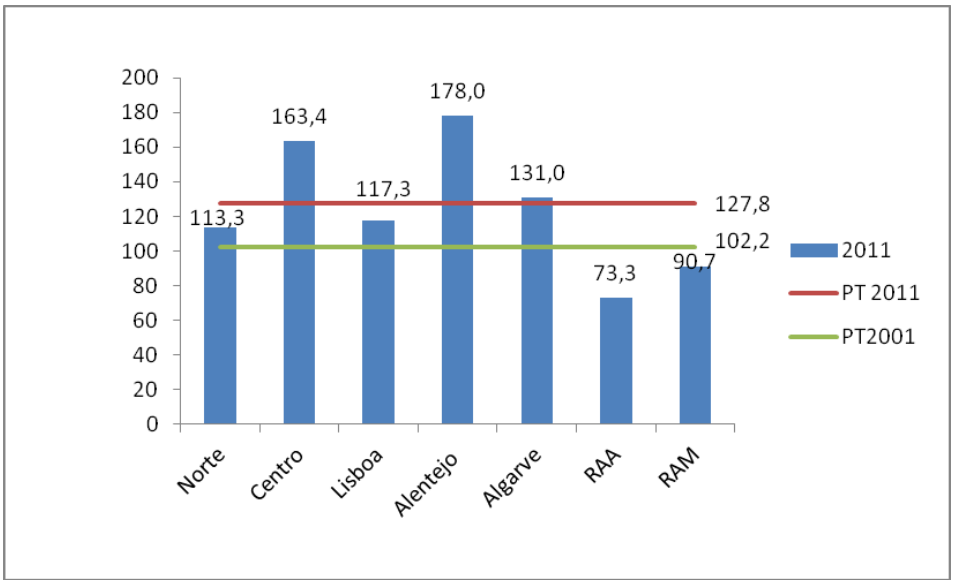

Índice de longevidade

O índice de longevidade, que relaciona a população com 75 ou mais anos com o total da população idosa com 65 ou mais anos era, em 2011, de 48, face a 41 em 2001 e 39 em 1991.

Em termos regionais, Lisboa apresentou o índice mais baixo (46), sendo o Alentejo a única região cujo índice ultrapassou 50, o que significa que a maior parte da sua população idosa tinha 75 ou mais anos.

Índice de longevidade, por NUTS II, 2001 e 2011

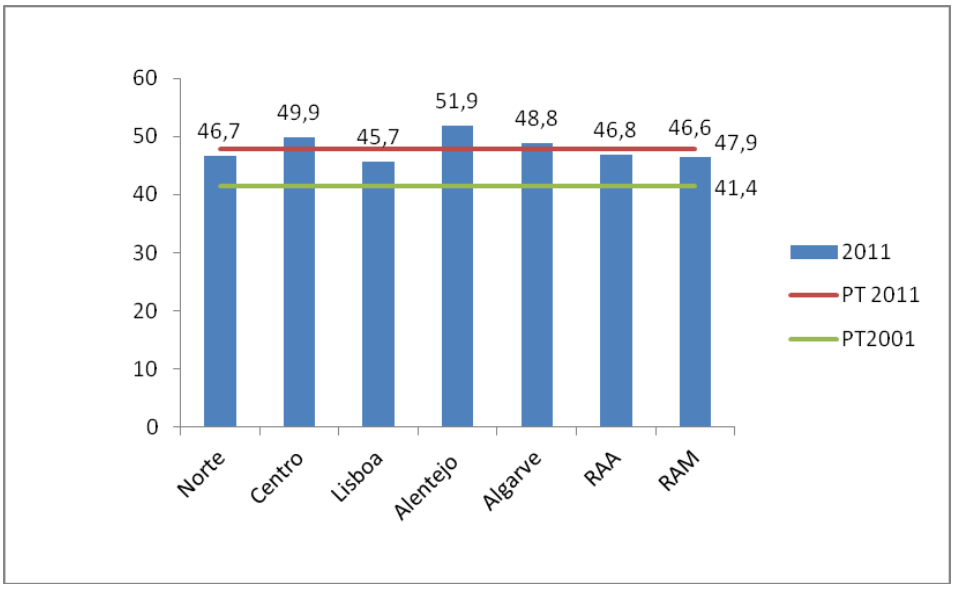

Índice de rejuvenescimento da população ativa

O índice de rejuvenescimento da população ativa era de aproximadamente 94, em 2011, o que significa que, potencialmente, por cada 100 pessoas que saíam do mercado de trabalho, entravam apenas 94. Este indicador agravou-se significativamente na última década, face à década anterior, em que atingiu 143, quando o número de pessoas a entrar no mercado de trabalho era significativamente superior ao número de pessoas que saía.

Em 2011 só as Regiões Autónomas apresentaram índices de rejuvenescimento superiores a 100.

Índice de rejuvenescimento da população ativa, por NUTS II, 2001 e 2011

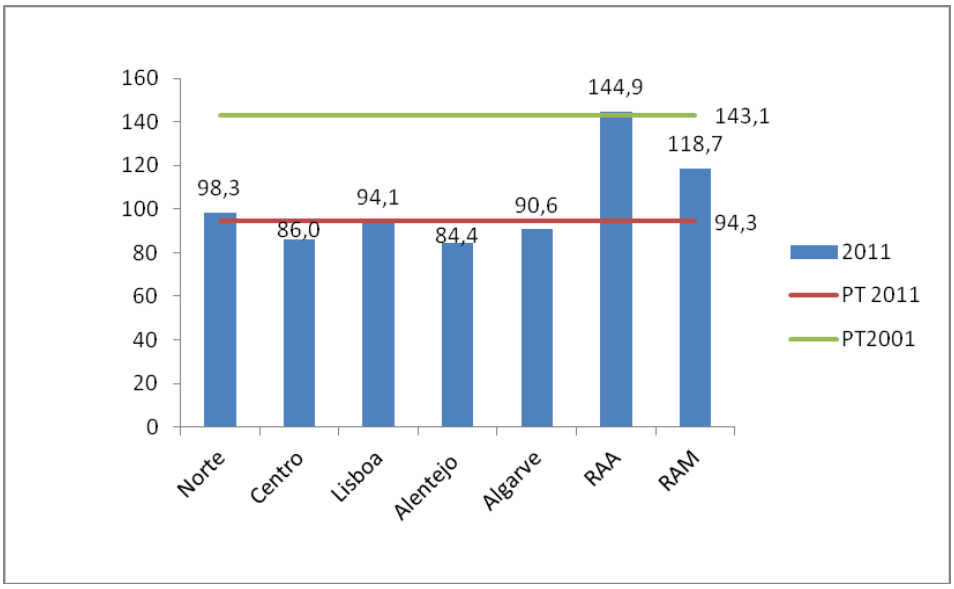

Índice de sustentabilidade potencial

Numa década, o número de indivíduos em idade ativa, por cada individuo idoso, passou de 4,1 em 2001, para 3,5 em 2011.

As Regiões Autónomas apresentaram os índices de sustentabilidade mais elevados: 5,3 para os Açores e 4,6 para a Madeira. No Alentejo e o Centro registaram-se os índices mais baixos, respetivamente 2,6 e 2,8.

Índice de sustentabilidade potencial, por NUTS II, 2001 e 2011

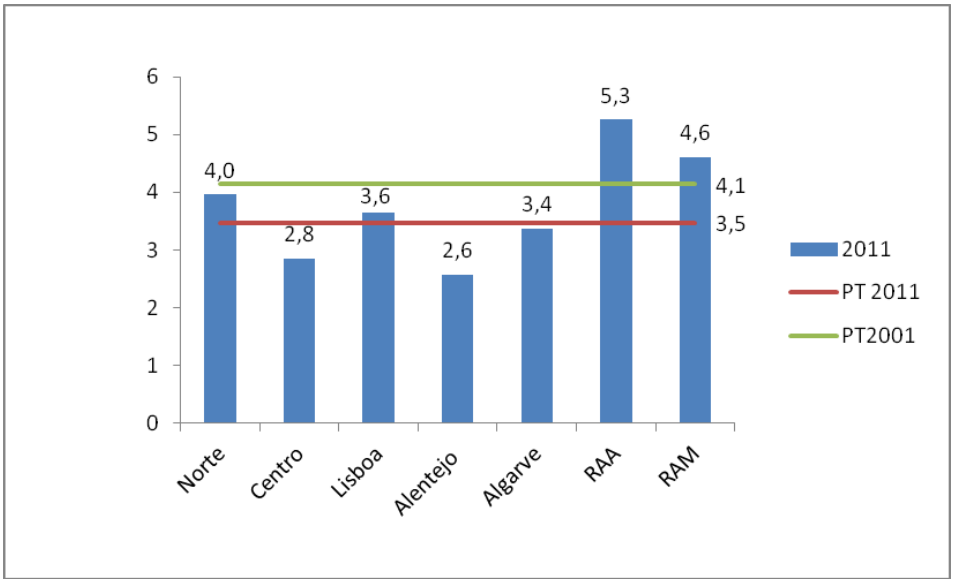

População de nacionalidade estrangeira

À data da realização dos Censos 2011, residiam em Portugal 394 496 pessoas de nacionalidade estrangeira, o que representava cerca de 3,7% do total da população.

Na última década, a população estrangeira cresceu cerca de 70%, já que era de 226 715 em 2001.

A maior comunidade estrangeira residente em Portugal era a brasileira, com 109 787 pessoas (cerca de 28%), seguindo-se a cabo-verdiana, com 38 895 (10%). A comunidade ucraniana era a terceira mais representada em Portugal, com 9%, surgindo a angolana em 4º lugar, com cerca de 7% (em 2001 ocupava o 1º lugar no conjunto da população estrangeira residente em Portugal, com um peso de 16%). Destaca-se, ainda, o aumento da população romena e chinesa verificado na última década.

Principais nacionalidades da população estrangeira residente em Portugal, 2011 e 2001

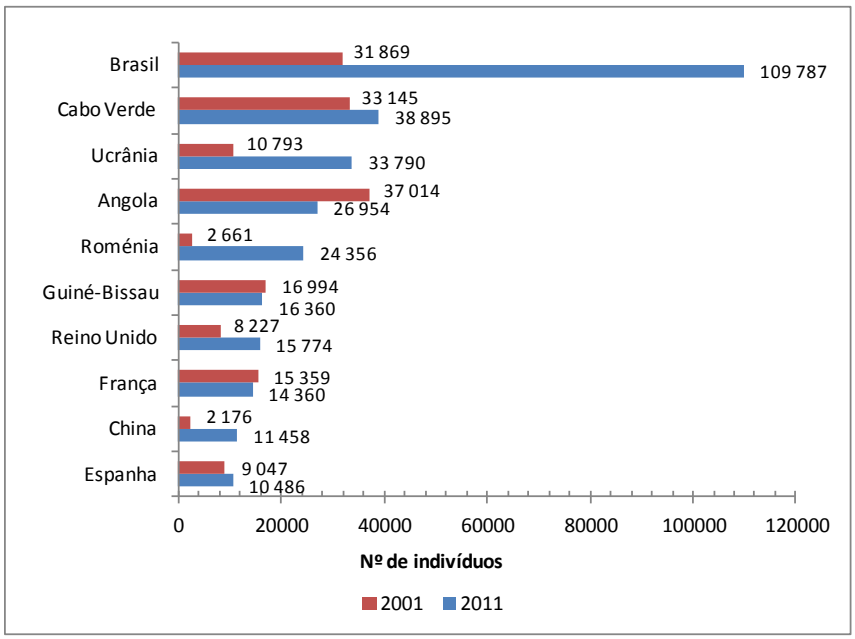

População estrangeira mais jovem do que a portuguesa

A estrutura etária da população estrangeira difere significativamente da estrutura da população portuguesa. De facto, na população estrangeira o maior grupo situa-se na população em idade ativa (15-64 anos), com 82%, enquanto na população nacional este grupo representa 66%. Adicionalmente, a população estrangeira idosa representa apenas 5%, contra 20% da população idosa portuguesa.

População portuguesa e estrangeira por grupo etário, 2011

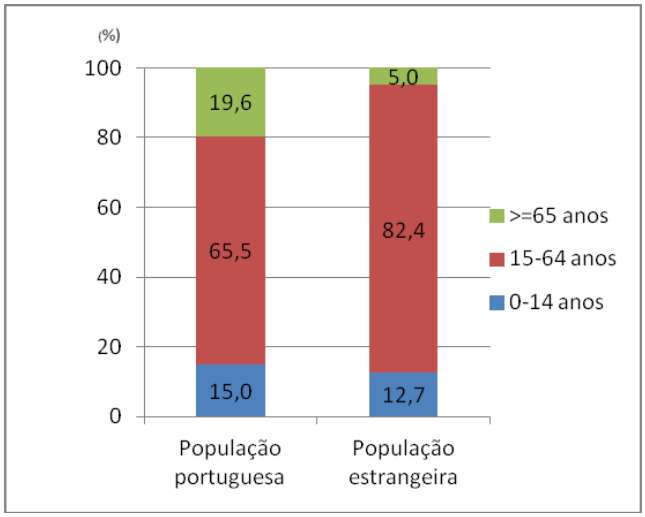

A população estrangeira era, em 2011, bastante mais jovem do que a portuguesa, com uma idade média de 34,2 anos, face a 42,1 da portuguesa.

A Região de Lisboa concentrava mais de metade dos estrangeiros a viver em Portugal

Em termos de distribuição geográfica, a Região de Lisboa concentrava mais de metade dos estrangeiros residentes em Portugal (51,6%), seguindo-se as regiões do Norte, Centro e Algarve todas com pesos na ordem dos 13%. As regiões com menos estrangeiros residentes eram as R.A. dos Açores e da Madeira onde residiam apenas 0,8% e 1,4% de estrangeiros.

População estrangeira residente em Portugal, por NUTS II, 2011

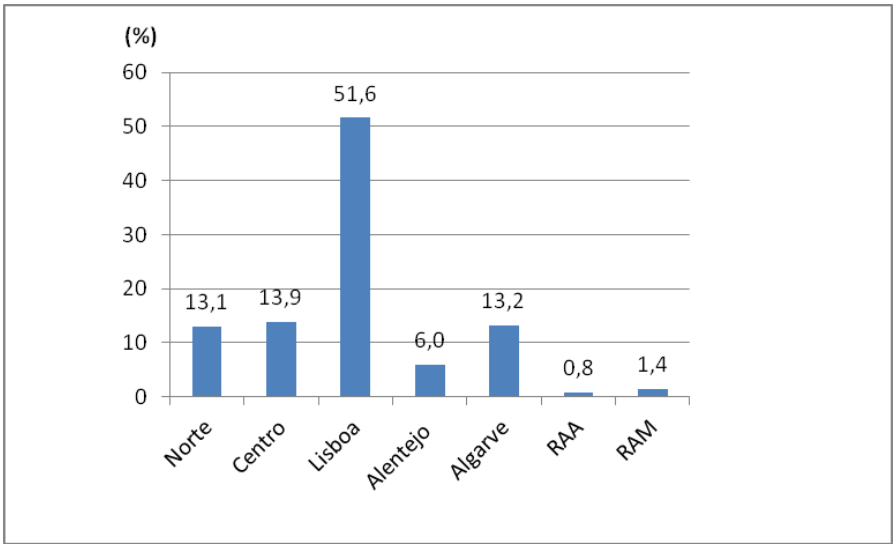

Estrangeiros são 12% da população do Algarve

Analisando a importância relativa dos estrangeiros face à população regional, verifica-se que era no Algarve que a população estrangeira tinha maior representatividade, representando cerca de 12% da população da região; seguia-se Lisboa, com 7%, o Alentejo com 3%, e a R.A. da Madeira e a Região Centro, ambas com valores da ordem dos 2%. Na R.A. dos Açores e na Região Norte a população estrangeira representava, respetivamente, 1,4% e 1,3% da sua população.

Importância relativa da população estrangeira na população residente, por NUTS II, 2011

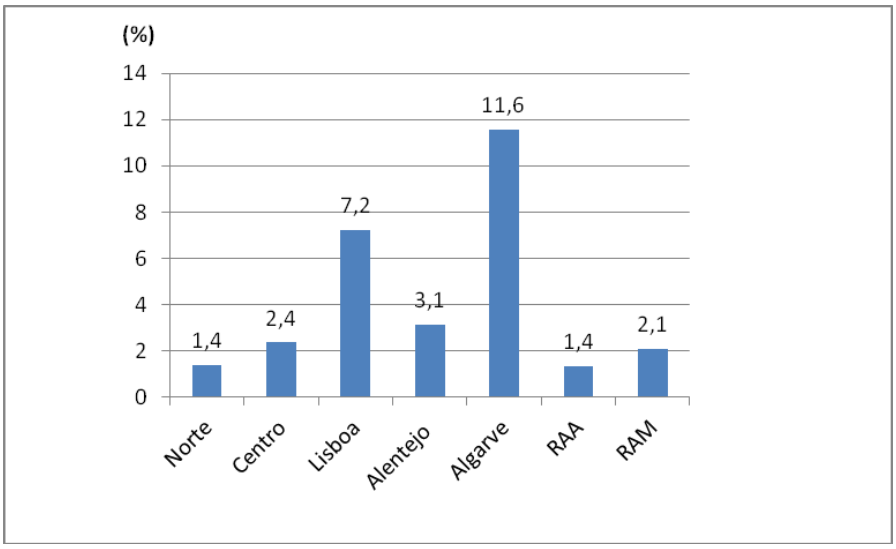

Os Portugueses que regressaram a Portugal

Cerca de 1,5 milhões de portugueses/as que viviam em Portugal em 2011 já tinham residido no estrangeiro, por um período contínuo de pelo menos um ano, tendo entretanto regressado a Portugal. Este valor é o reflexo da importância que o fenómeno emigratório teve na sociedade portuguesa ao longo das últimas quatro décadas.

Os mais representativos países de proveniência desta população são França, com 26% e Angola com 15%, seguindo-se-lhes Moçambique (7,8%), Alemanha (7,6%) e Suíça (7,2%). Neste conjunto é possível identificar por um lado alguns dos países de destino tradicional da emigração portuguesa e, por outro, o retorno decorrente do processo de descolonização.

População de nacionalidade portuguesa que já residiu no estrangeiro, por último país onde residiu

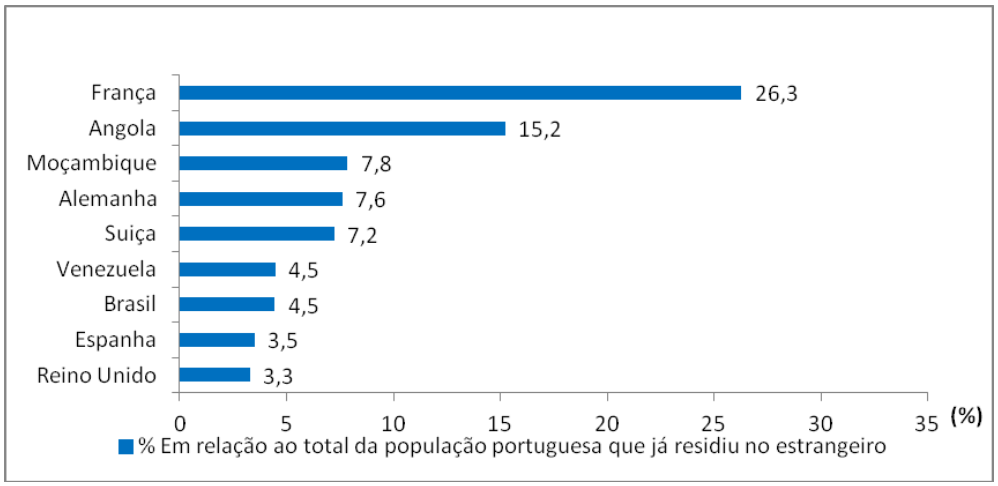

De facto, foi durante o período 1971-1980 que se registou o regresso de maior número de emigrantes a Portugal, intimamente relacionado com o regresso de cidadãos portugueses das ex-colónias.

Uma segunda vaga no regresso da população emigrante a Portugal, ocorreu durante as décadas de 80 e 90, principalmente associada è emigração tradicional.

População de nacionalidade portuguesa que já residiu no estrangeiro, por ano de regresso a Portugal

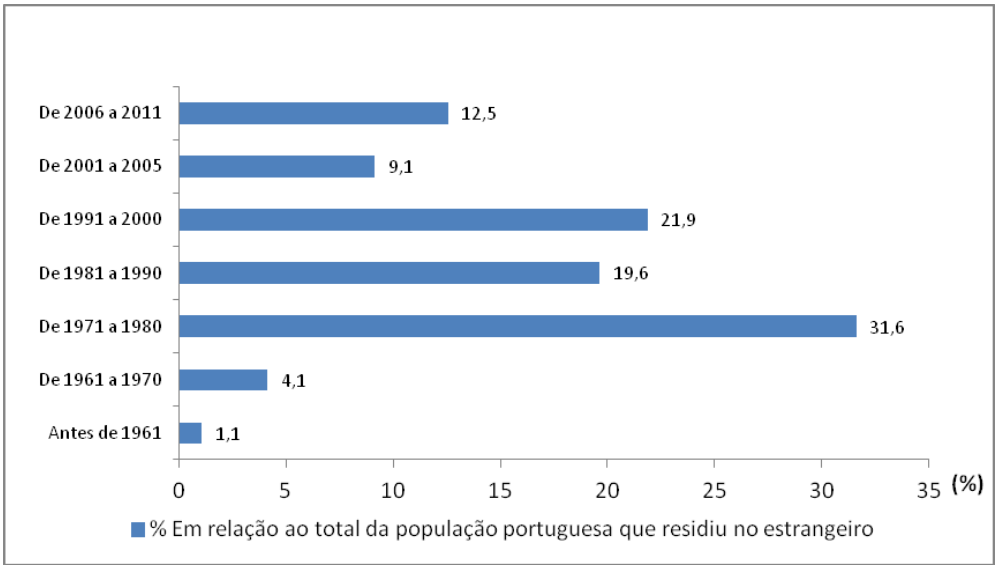

Estado civil e conjugalidade

Embora em 2011 as uniões conjugais continuassem a ser maioritariamente formalizadas através do casamento (87%), as uniões de facto já representavam cerca de 13% do total face a 7% em 2001.

Na Região do Algarve as uniões de facto representam cerca de 21% das uniões conjugais, peso que atingia 20% em Lisboa e 14% no Alentejo. O valor mais baixo, de cerca de 9%, registava-se na Região Norte.

Proporção da população que vive em união de facto, por NUTS II, 2001 e 2011

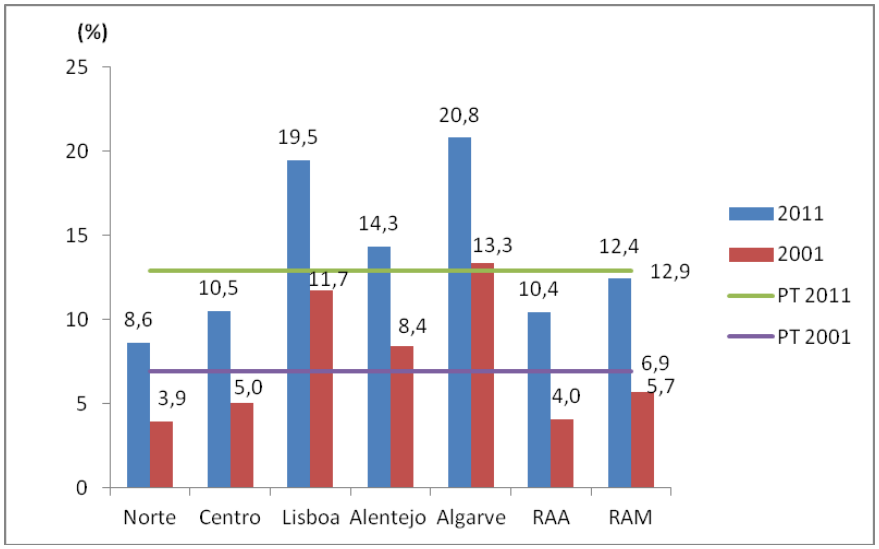

Cerca de 47% da população recenseada nos Censos 2011 era casada. O grupo dos/as solteiros/as representava 40% e os viúvos/as e divorciados/as representavam respetivamente 7% e 6%.

Estado civil legal da população residente, 2011

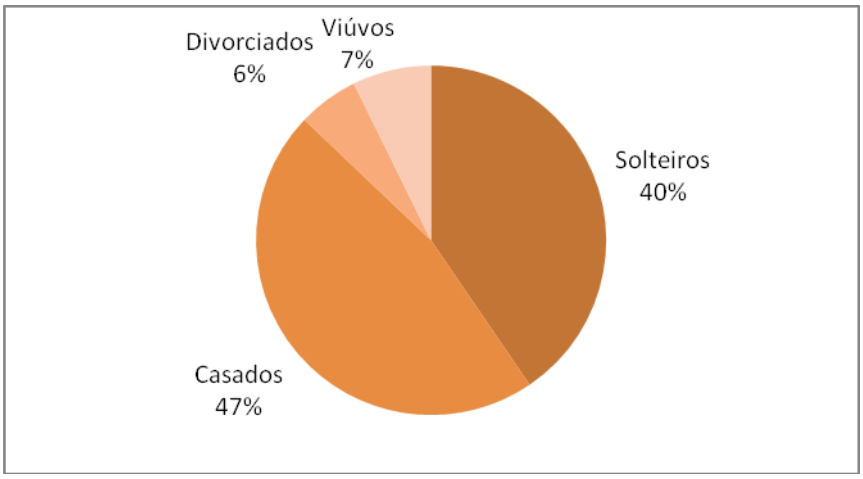

A análise do estado civil por sexo evidencia algumas diferenças entre homens e mulheres. Assim:

Os homens são:

48% casados;

44% Solteiros;

5% divorciados;

3% viúvos.

As mulheres são

45% Casadas;

38% solteiras;

6% divorciadas;

11% viúvas.

População com dificuldades na realização de algumas atividades do dia a dia por motivos de saúde ou idade

Mais de 82% da população com 5 ou mais anos consideraram não ter dificuldade em realizar atividades diárias relacionadas com a visão, audição, locomoção, memória/concentração e com a higiene e arranjo pessoal e, ainda, em compreender os outros e fazer-se entender por eles.

Assim, apenas cerca de 18% da população com 5 ou mais anos de idade declarou ter muita dificuldade, ou não conseguir realizar pelo menos uma das 6 atividades diárias. Contudo, na população com 65 ou mais anos, este indicador ultrapassava 50%.

A dificuldade em andar era a principal limitação na realização das tarefas diárias. De facto, das pessoas com 5 ou mais anos que tinham pelo menos uma dificuldade, 25% não conseguiam ou manifestavam muita dificuldade em andar ou subir degraus.

Por outro lado, cerca de 23% tinham muita dificuldade ou não conseguiam ver mesmo usando óculos ou lentes de contacto.

Tipo de dificuldade na realização das atividades diárias, em 2011

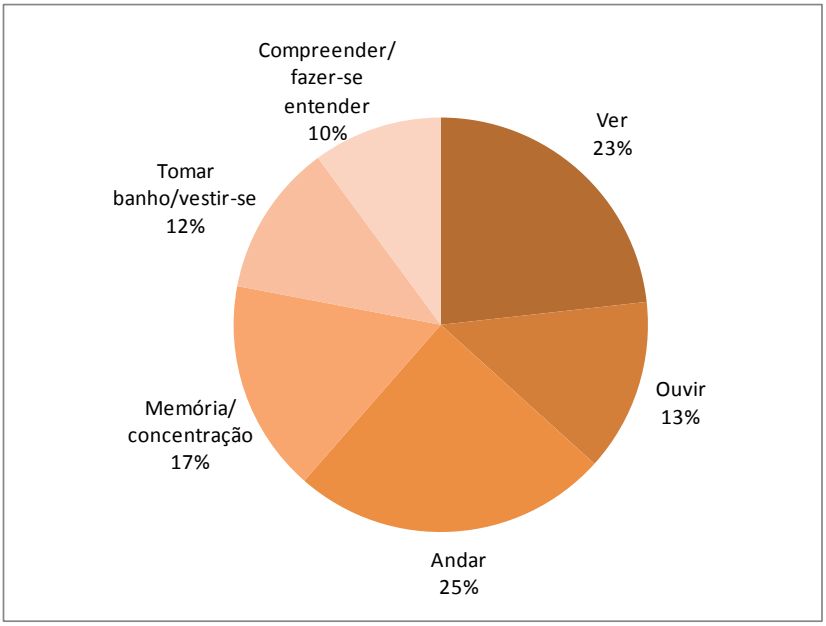

Nível de escolaridade

Na última década, o país registou progressos muito significativos em todos os níveis de ensino.

- A população com 23 ou mais anos com ensino superior passou de 9% em 2001 para 15%, em 2011, tendo o número de diplomados quase duplicado e atingido 1 244 742, 60% dos quais mulheres;
- A população com 15 ou mais anos com pelo menos o 9º ano aumenta para 50%, sendo 38% em 2001;
- A taxa de analfabetismo recuou de 9% em 2001 para 5,2% em 2011.

A população com Ensino Superior completo

Na **Região de Lisboa** residiam 21% das/os diplomadas/os do país, seguindo-se-lhe as regiões Norte, Centro, Algarve e R.A. da Madeira com 13% cada e Alentejo e R.A. dos Açores com 11%.

Proporção da População com 23 ou mais anos com o Ensino Superior completo, em 2001 e 2011

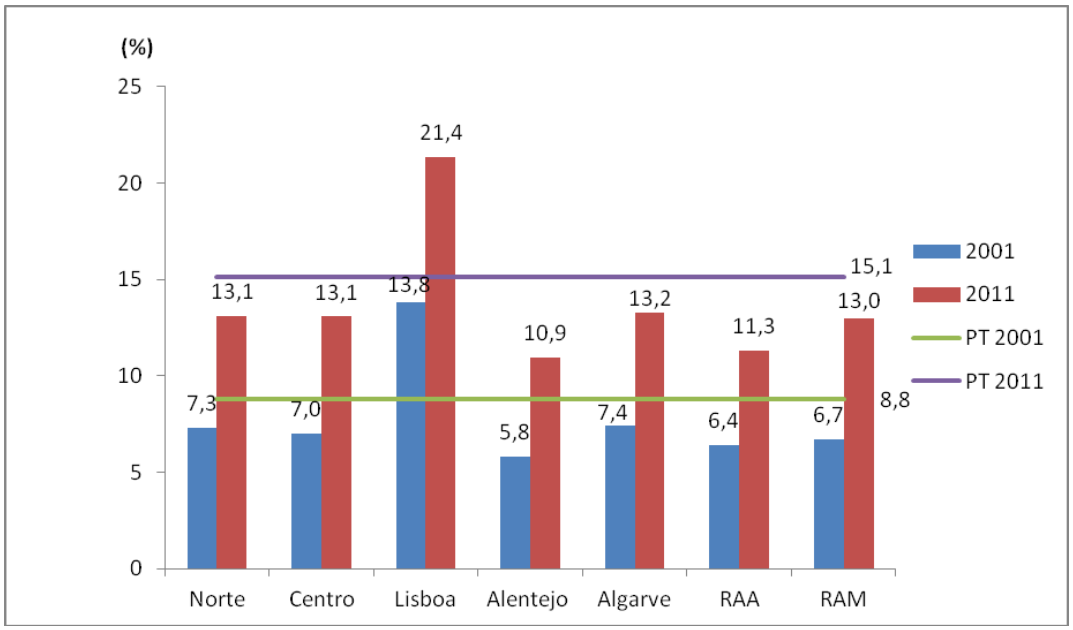

Mais de 50% dos diplomados concentravam-se em 4 grandes áreas de estudo: Comércio e Administração (14,5%); Formação de professores/as (13,6%), Saúde (13,4%) e Ciências sociais (10%), facto que representa algumas modificações face à situação registada em 2001, tendo-se reforçado a importância dos cursos nas áreas de Saúde, Ciências informáticas e Formação de professores. Em contrapartida perderam relevância as áreas das Letras e Ciências religiosas, Direito e Agricultura.

Em 2011, a percentagem da população com cursos na área de engenharia era de 7,6% e em ciências informáticas de 3%.

População com ensino superior, por áreas de estudo, em 2001 e 2011

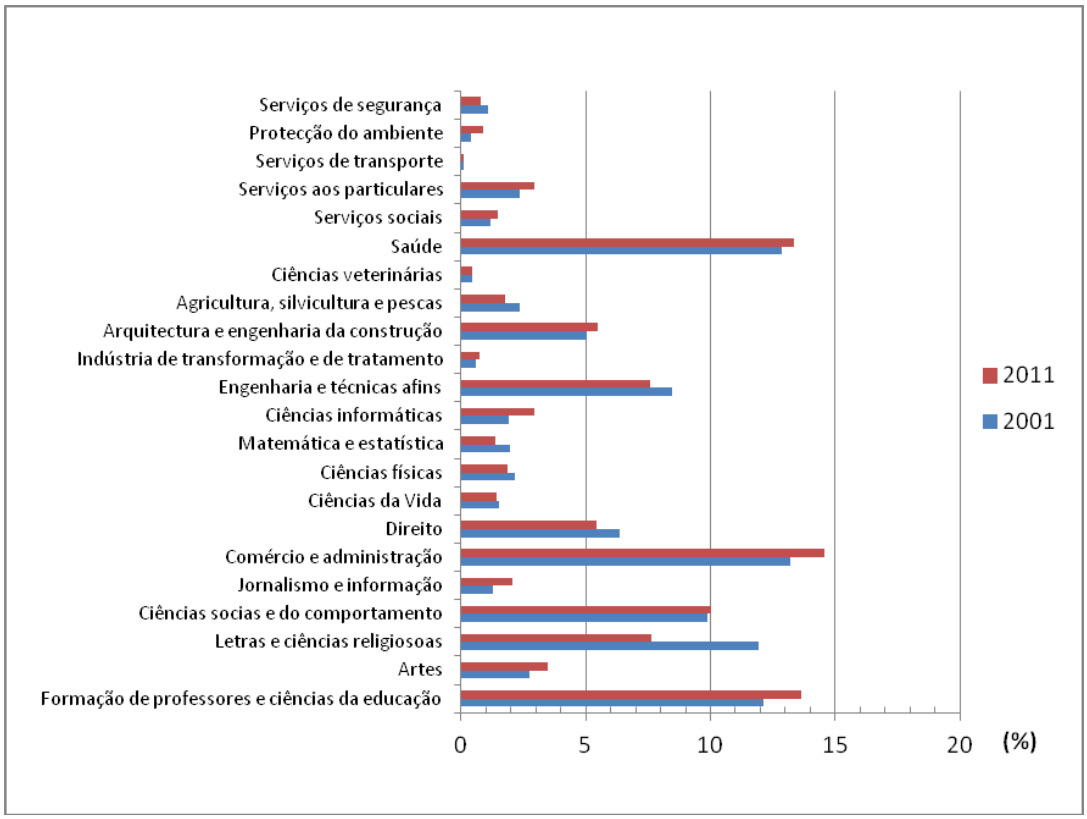

As mulheres eram predominantes na maior parte das áreas de estudo. As exceções verificavam-se nas áreas da engenharia (78% de licenciados homens), das ciências informáticas (76% de licenciados homens), da arquitetura (67% de licenciados homens), agricultura (59% de licenciados homens) e do comércio e administração (57% de licenciados homens).

Na população feminina predominavam as diplomadas em Formação de Professores/as, Saúde, Comércio e Administração, Ciências Sociais, Letras e Ciências Religiosas e Direito. Nos diplomados predominavam as áreas do Comércio e administração, Engenharia e Arquitetura.

População masculina, com ensino superior, por área de estudo, 2011

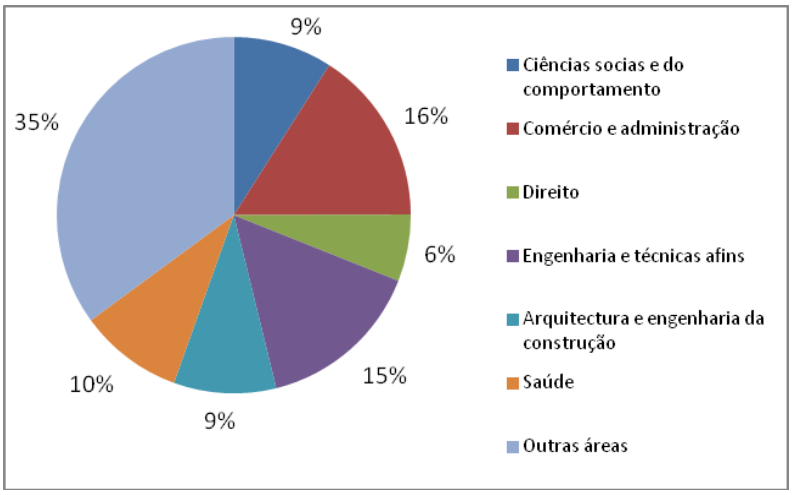

População feminina, com ensino superior, por área de estudo, 2011

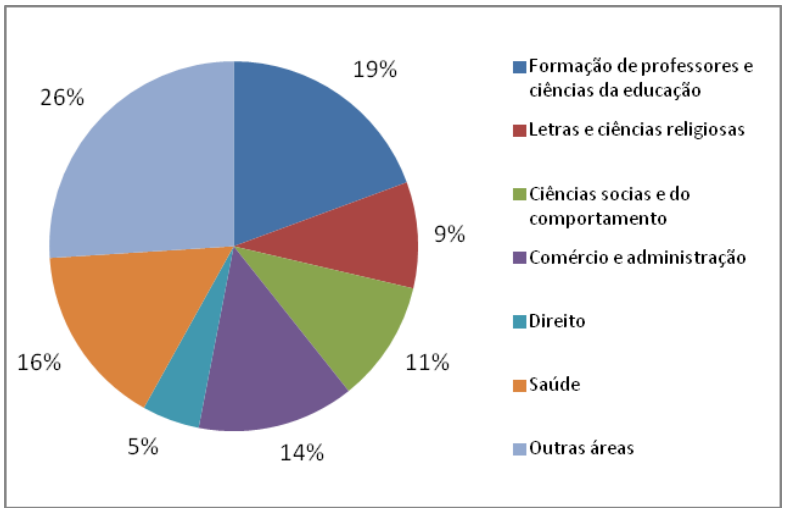

População com o 9º ano

A população com 15 ou mais anos que completou o 9º ano de escolaridade atingia, em 2011, 4 459 152, ou seja, cerca de 50% do grupo etário correspondente, ou seja mais 12 pontos percentuais do que em 2001. Apenas nas Regiões de Lisboa (60%) e do Algarve (53%), este indicador apresenta valores acima dos 50%. Nas restantes regiões, a proporção da população com o 9º ano varia entre os 42% na Região Autónoma dos Açores e os 46% na Região Centro.

A proporção de homens e mulheres neste grupo etário era muito semelhante, rondando os 50%.

Proporção da população com 15 ou mais anos, com pelo menos o 9º ano, por NUTS II, 2001 e 2011

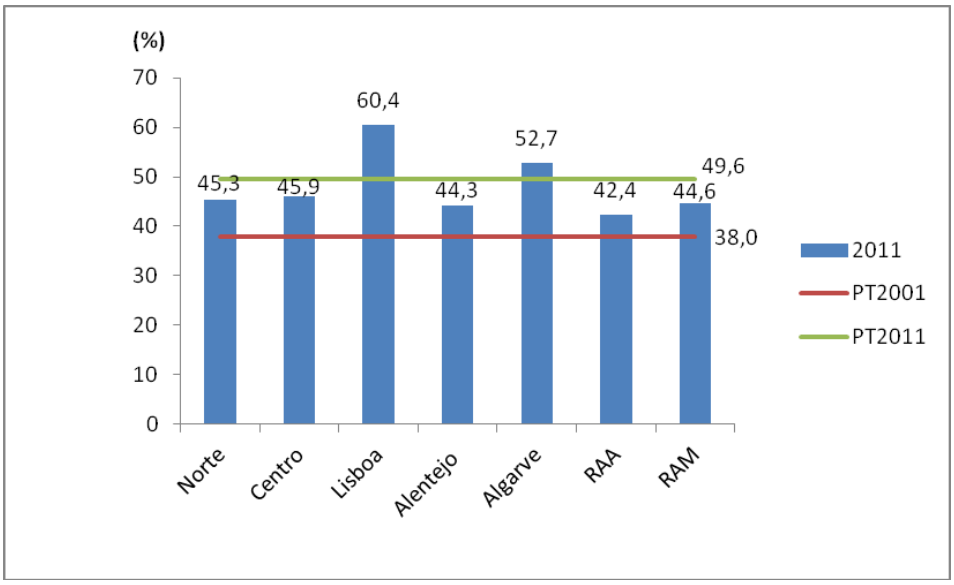

Analfabetismo

A taxa de analfabetismo, expressa pela relação entre a população, com 10 ou mais anos, que não sabe ler e escrever e a população com 10 ou mais anos, recuou de forma significativa nas últimas décadas, passando de 11% em 1991, para 9% em 2001 e 5,2% em 2011.

Em 2011, a taxa de analfabetismo das mulheres era bastante superior à da taxa de analfabetismo dos homens, isto é, 6,8% e 3,8% respetivamente.

A população analfabeta era essencialmente idosa, 79% com mais de 65 anos, continuando a registar-se grandes assimetrias regionais. Em 2011, com 3,2% de analfabetos, Lisboa registava a taxa de analfabetismo mais baixa. Na situação oposta encontrava-se a Região do Alentejo, com 9,6% de taxa de analfabetismo.

De referir que, em 2011, cerca de 10% da população com 15 ou mais anos não tinha qualquer nível de escolaridade completo (18% em 2001).

Alguns indicadores sobre o nível de escolaridade

	2001	2011
Taxa de Analfabetismo	9,03	5,23
Proporção de Crianças 3-5 anos a frequentar o Ensino Pré-Escolar	52,28	73,49
Proporção da População com 15 ou mais anos sem qualquer nível de escolaridade completo	18,03	10,39
Proporção de Jovens 18-24 anos que completou no máximo o 3º Ciclo (9º ano) e que não estão a estudar	33,37	22,08
Proporção de Jovens 20-24 anos que completou pelo menos o Ensino Secundário	44,04	60,80
Proporção da População 30-34 anos que completou o Ensino Superior	14,22	28,62
Proporção da População com 15 ou mais anos que completou pelo menos o 3º Ciclo do Ensino Básico (9º ano)	37,95	49,60
Proporção da População com 18 ou mais anos que completou pelo menos o Ensino Secundário	22,67	31,69
Proporção da População com 23 ou mais anos que completou o Ensino Superior	8,81	15,11

Caracterização socioeconómica

Perante a atividade económica, em 2011, 42% da população total encontrava-se na situação de empregada, 6% na condição de desempregada e 52% na situação de inatividade.

A população reformada e a população com menos de 15 anos representavam, respetivamente, 32% e 29% do total da população em situação de inatividade. Os restantes 29% abrangia população com menos de 15 anos, estudantes com 15 ou mais anos, domésticos/as e outra.

Condição perante a atividade económica da população residente, em 2011

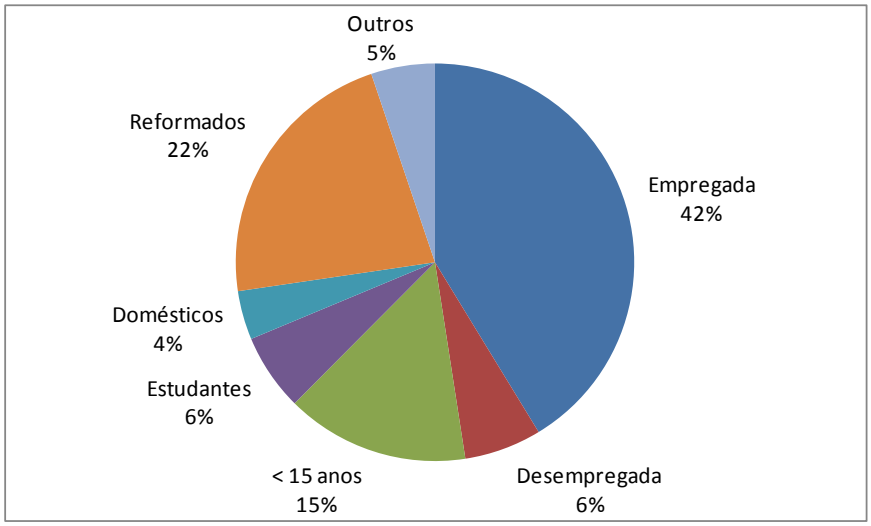

A representação dos homens e das mulheres é diferente consoante os grupos que compõem a condição perante a atividade económica:

- Na população empregada há 52% de homens e 48% de mulheres
- Na população reformada há 49% de homens e 51% de mulheres
- Na população "domésticos" há 2% de homens e 98% de mulheres

Condição perante a atividade económica, segundo o sexo, em 2011

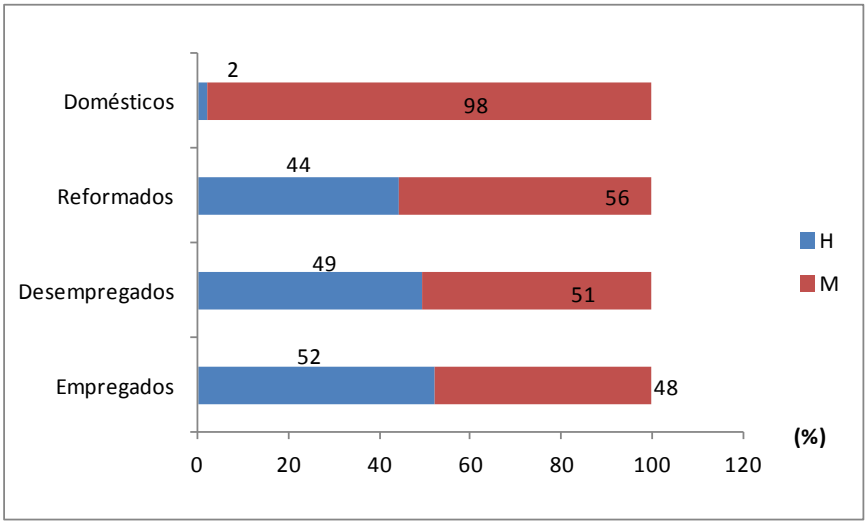

Principal fonte de rendimento

De acordo com os resultados dos Censos 2011, para 48% da população residente com 15 ou mais anos, a principal fonte de rendimento nos 12 meses, que antecederam o momento censitário foi o trabalho, seguindo-se as pensões e reformas para 27% da população. 18% da população com 15 e mais anos vivia a cargo da família.

O Subsídio de Desemprego e o Rendimento Social de Inserção foram, respetivamente, a principal fonte de rendimento para 3,3% e 1,1% da população residente com 15 ou mais anos.

Principal meio de vida da população com 15 ou mais anos, em 2011

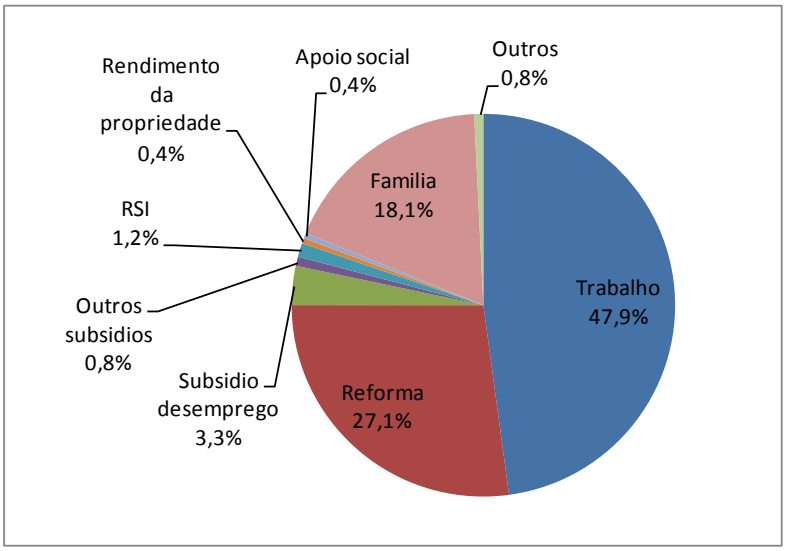

Emprego, horário de trabalho, profissão e ramo de atividade

De acordo com os resultados dos Censos 2011, a população empregada em Portugal era de 4 361 187 pessoas, sendo 52,2% homens e 47,8% mulheres.

A maior parte da população (81,2%) trabalhava por conta de outrem; Cerca de 18% dos/as trabalhadores/as por conta de outrem cumpriam um horário semanal de 45 ou mais horas e 8% de menos de 30 horas.

Vendedores/as em lojas, empregados/as de escritório, trabalhadores/as de limpeza e da construção e professores/as do ensino básico e secundário representavam um quarto da população empregada.

Principais subgrupos de profissões da população empregada, em 2011

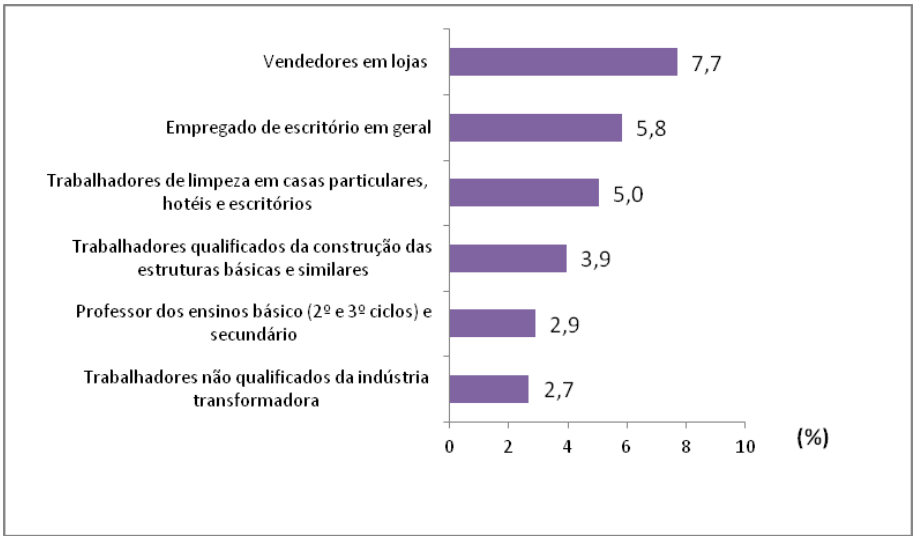

Cerca de 70% do emprego estava alocado às atividades de serviços. Neste sector, os grupos de atividade económica "comércio, alojamento, transportes e comunicações" com 30% e "outras atividades de serviços" com 29% eram os que mais pessoas empregavam. As atividades financeiras, imobiliárias e serviços às empresas concentravam cerca de 11% do emprego.

O emprego na indústria e a construção civil recuou entre 2001 e 2011 representando, neste último ano, respetivamente 18% e 9% da mão-de-obra total empregada.

A agricultura e pescas voltaram a perder importância e representavam, em 2011, apenas 3% da população empregada.

População empregada, segundo os principais grupos de atividade, em 2001 e 2011

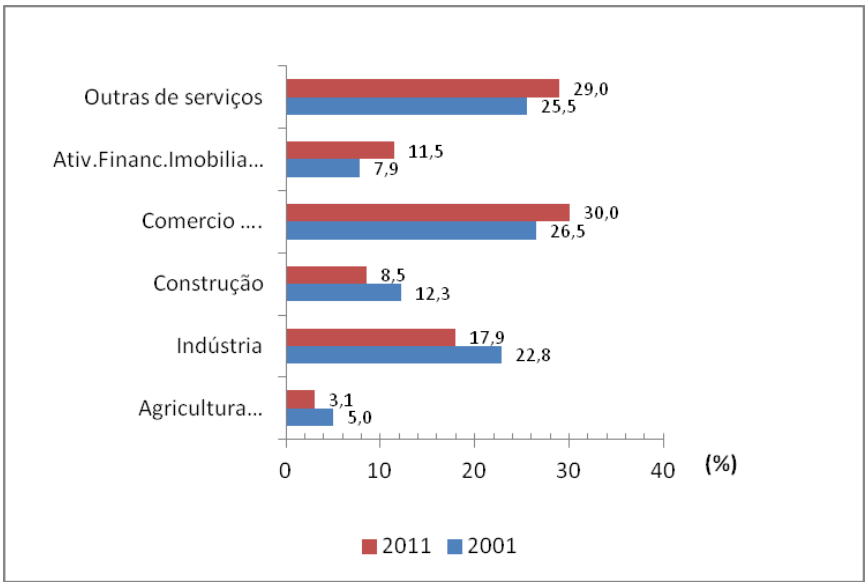

Movimentos pendulares

De acordo com os resultados definitivos dos Censos 2011, o movimento pendular de entrada de população nos municípios de Lisboa e do Porto, por razões de trabalho ou estudo, abrangia 425 737 e 171 738 pessoas, o equivalente a 77,7% e 72,3% da respetiva população residente.

No conjunto dos 10 municípios mais populosos, o de Braga distingue-se também pela predominância dos movimentos pendulares de entrada (58% do total).

Nos restantes 7 municípios do grupo dos mais populosos do País o sentido do movimento pendular mais significativo era o de saída de pessoas: em Sintra, Loures e Amadora, cerca de 30% da população residente deslocava-se para fora do município por razões, de trabalho ou estudo, proporção que em Almada, Matosinhos, Cascais e Vila Nova de Gaia se situava entre 20 e 25%.

Movimentos pendulares: entradas e saídas nos 10 municípios com mais população, em 2011

Municípios	População residente	Nº pessoas que entravam	% Entradas em relação à população residente	Nº pessoas que saíam	% Saídas em relação à população residente
Lisboa	547 733	425 747	77,73	47 521	8,68
Porto	237 591	171 738	72,28	28 899	12,16
Matosinhos	175 478	34 785	19,82	43 893	25,01
Amadora	175 136	30 432	17,38	57 484	32,82
Almada	174 030	29 081	16,71	42 090	24,19
Loures	205 054	33 839	16,50	62 627	30,54
Braga	181 494	28 347	15,62	20 309	11,19
Cascais	206 479	24 401	11,82	50 528	24,47
V.N.Gaia	302 295	27 186	8,99	62 050	20,53
Sintra	377 835	31 825	8,42	110 107	29,14

Movimentos pendulares: entradas e saídas em % da população residente, nos 10 municípios com mais população, em 2011

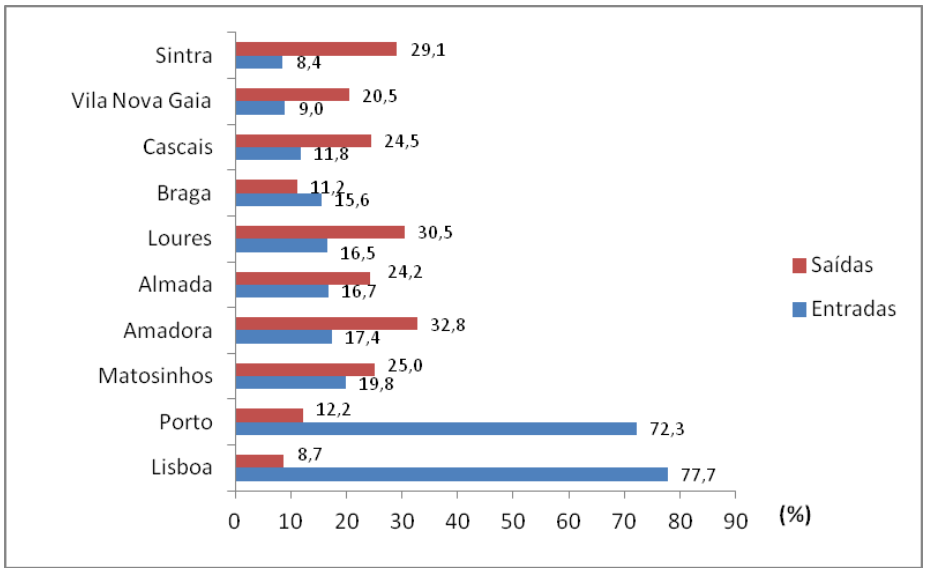

Meio de transporte

O automóvel é o meio de transporte mais utilizado pela população nas deslocações casa-trabalho ou casa-estudo. Cerca de 62% da população, que diariamente se desloca para a realização das suas atividades, opta pelo automóvel, quer como condutor, quer como passageiro, mais 16 pontos percentuais do que em 2001.

Nas áreas metropolitanas de Lisboa e Porto essa percentagem é de 54,0% e 62,7%, respetivamente.

No quadro do transporte coletivo, só o metropolitano reforçou a sua importância nas deslocações pendulares. Em 2011, de facto, 105 591 pessoas indicaram usar preferencialmente este meio de transporte, face a 38 079 em 2001. O autocarro continuou a ser o transporte público mais utilizado pela população, mas a sua importância recuou cerca de 4 pp na última década.

Meio de transporte utilizado nos movimentos pendulares, em % da população, 2001 e 2011

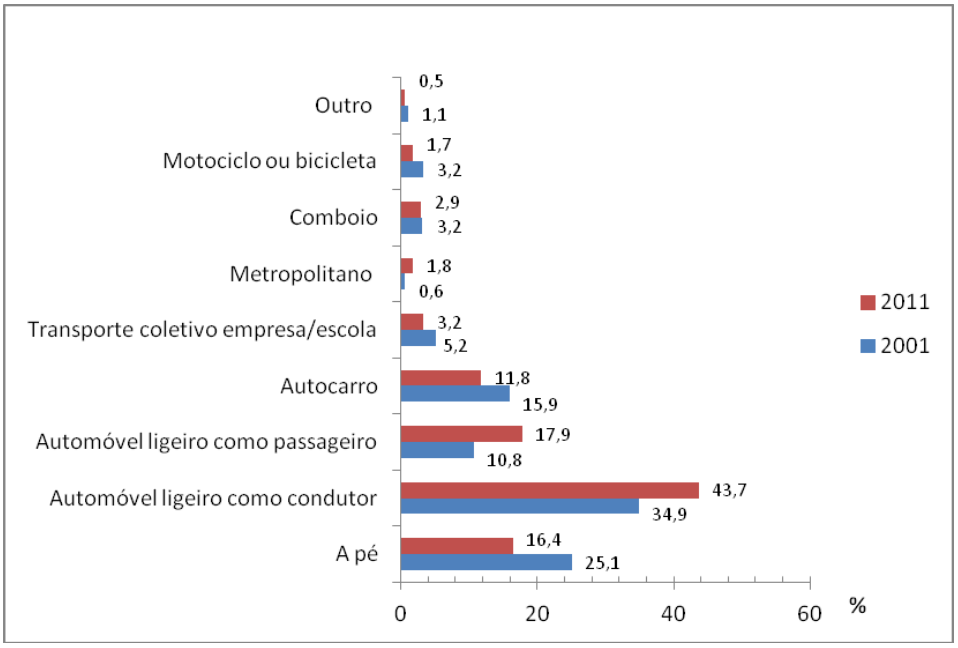

Em 2011, o tempo médio para chegar ao local de trabalho ou estudo era de 20 minutos, demorando mais de metade da população menos de 15 minutos. . Nas áreas metropolitanas de Lisboa e Porto esse tempo médio era de 26,37 minutos para Lisboa e de 19,87 minutos para o Porto.

População por tempo médio de deslocação, 2001 e 2011

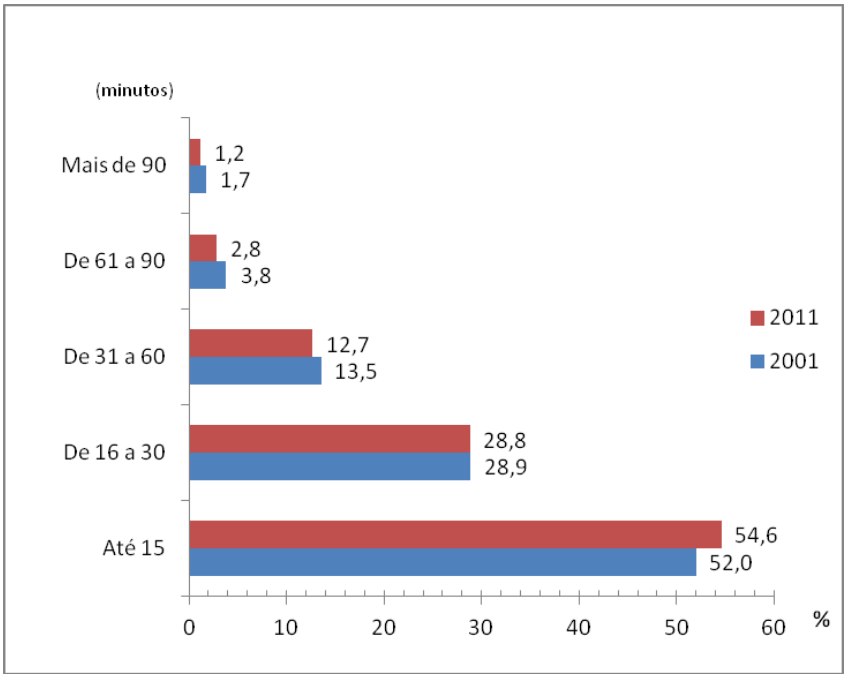

Famílias

Na última década, acentuaram-se as transformações que se vinham verificando ao nível da Família e do lugar que esta ocupa na sociedade.

Entre 2001 e 2011, o número de famílias clássicas aumentou cerca de 11%, atingindo as 4 043 726. Esta evolução decorre não só do crescimento da população, mas também da influência de outros fatores sociodemográficos, como as alterações nos padrões de nupcialidade, a divorcialidade e a fecundidade, bem como do aumento da esperança média de vida que concorrem para as alterações verificadas ao nível das estruturas familiares.

As famílias são hoje mais pequenas

A dimensão média das famílias era de 2,6, em 2011, enquanto em 2001 era de 2,8. As R.A. dos Açores e da Madeira e a Região Norte, com 3,0 pessoas por família, apresentavam os valores mais elevados. Lisboa, Alentejo e Algarve tinham as famílias menos numerosas, com 2,4 elementos.

Aumentou o número de pessoas que vivem sós

As famílias clássicas constituídas por uma só pessoa representavam, em 2011, cerca de 21% do total de famílias, tendo o seu número vindo a aumentar nas últimas décadas. Em 2011, foram recenseadas 866 827 famílias unipessoais, contra as 631 762 apuradas em 2001.

O número de famílias unipessoais constituídas por uma pessoa idosa representava a maior parte das famílias unipessoais e correspondia a cerca de 10% do total de famílias clássicas.

As famílias unipessoais concentravam-se, predominantemente, nos territórios do interior, em geral com índices de envelhecimento mais elevados.

Dimensão médias das famílias, em 2001 e 2011

Dimensão média das famílias, por NUTS II, em 2011

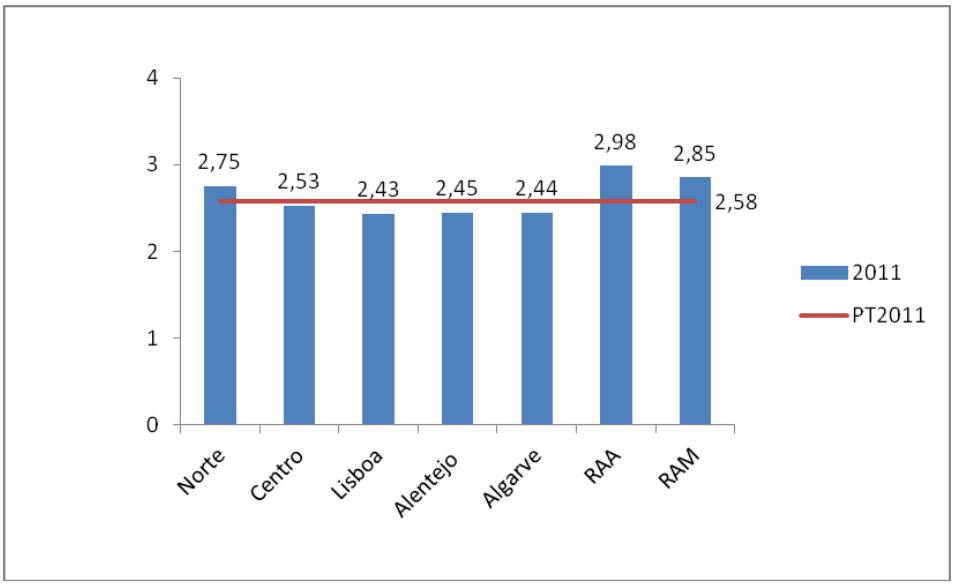

A estrutura familiar predominante continuava a ser a de "casal com filhos", apesar de perder importância relativa

Em 2011 o número de núcleos familiares "casal com filhos" era de 1 614 290, em queda face ao registado em 2001, em que estes núcleos eram 1 740 522.

A proporção de casais com filhos, 50% em 2011, recuou cerca de 7 pp na última década. Esta proporção não se verificou apenas na Região Norte e as Regiões Autónomas, onde a proporção de núcleos familiares "casais com filhos" se situava acima de 50%.

Núcleos familiares segundo o Tipo de Núcleo, em 2001 e 2011

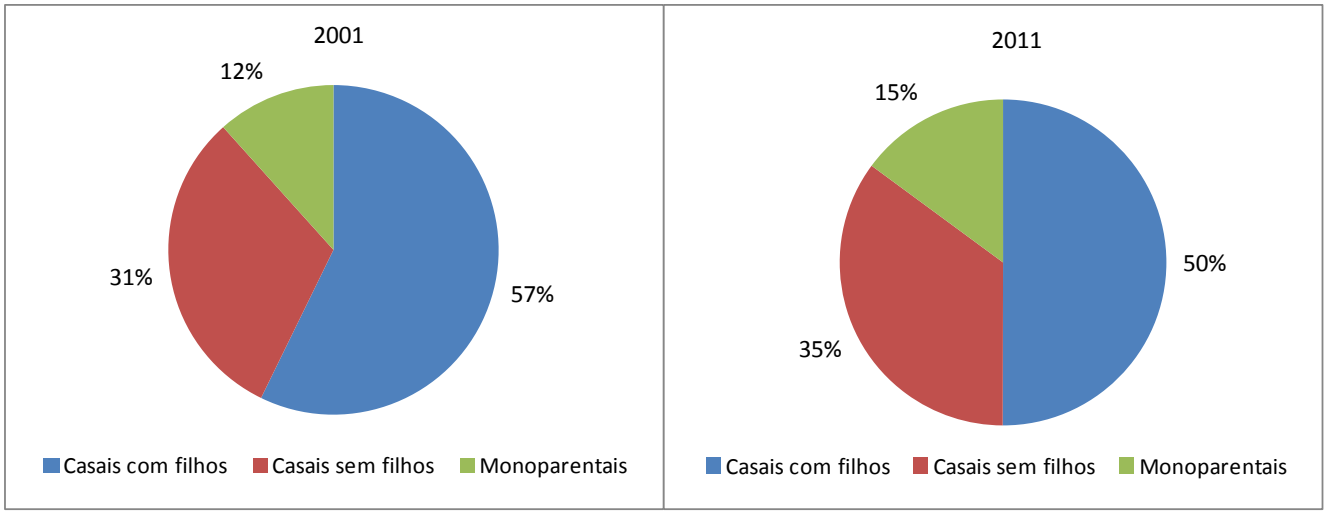

Núcleos familiares monoparentais aumentam significativamente

Em 2011, foram recenseados 480 443 núcleos familiares monoparentais, o que representa um crescimento de cerca de 36% face a 2001.

O aumento da proporção de núcleos familiares monoparentais, no total de núcleos familiares, revela a alteração do modelo de vivência familiar que tem vindo a operar-se na sociedade portuguesa nos últimos anos.

Proporção de núcleos monoparentais no total de núcleos, por NUTS II, em 2011

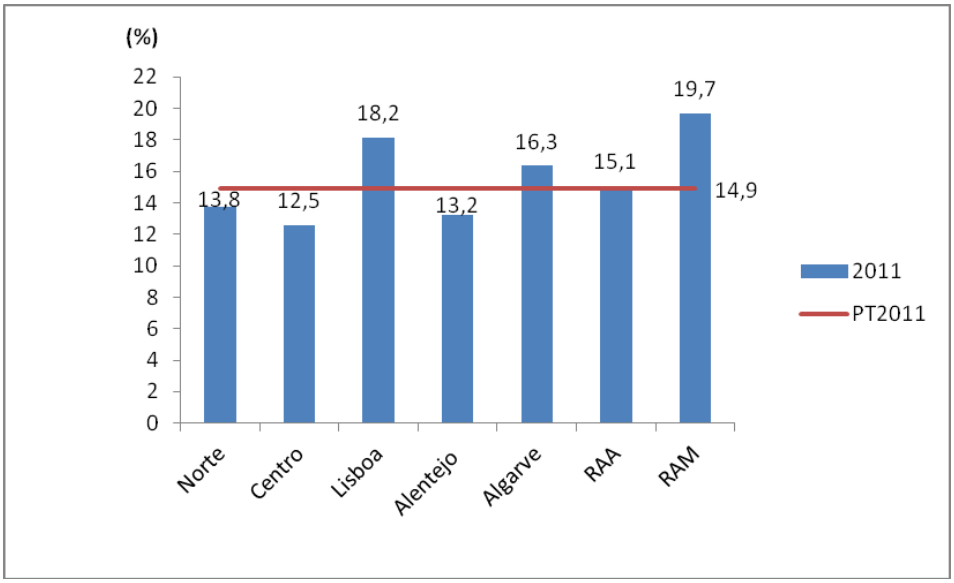

À semelhança do que se verificara ao longo da década de 90, os núcleos monoparentais constituídos por mãe com filhos continuam, na primeira década do milénio, a prevalecer face ao número de núcleos de pai com filhos, representando mais de 86% do total de núcleos monoparentais (416 343 e 64 100 respetivamente).

Em termos regionais, a R.A. da Madeira apresentava 20% do total de núcleos familiares monoparentais, a proporção mais elevada do País, seguindo-se-lhe Lisboa, com 18%.

Núcleos familiares reconstituídos (famílias recompostas) mais que duplicam

Em 2011, o número de núcleos familiares reconstituídos ascendeu a 105 764, o que representa um crescimento muito significativo em relação a 2001 (46 786).

Este crescimento revela também a emergência das novas formas de organização familiar, em resultado dos padrões recentes de nupcialidade e fecundidade.

Os núcleos familiares reconstituídos representam cerca de 7% do total dos núcleos familiares de casais com filhos.

Núcleos reconstituídos, por NUTS II, em 2011

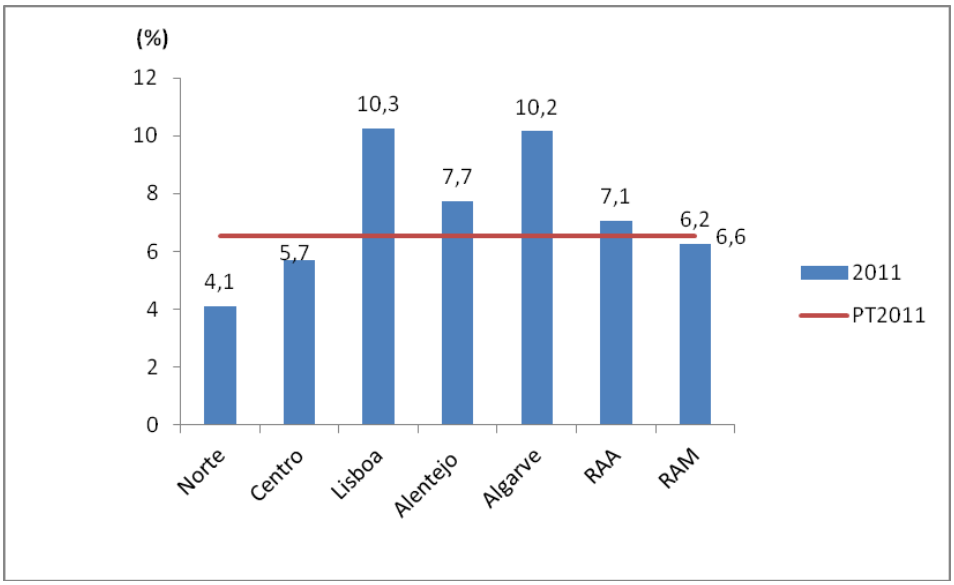

É nas Regiões do Algarve e de Lisboa que se verificava a maior incidência deste tipo de organização da família, com cerca de 10%. Na Região Norte os núcleos familiares reconstituídos representavam apenas 4%.

A importância relativa dos núcleos familiares reconstituídos aumentou em todas as regiões, oscilando este acréscimo entre 2,6 pontos percentuais na Região Norte e 6,0 na Região de Lisboa.

Parque habitacional

Na última década, manteve-se um forte crescimento do parque habitacional

De acordo com os resultados dos Censos 2011, o número de edifícios destinados à habitação era de 3 544 389 e o de alojamentos de 5 878 756, valores que, face a 2001, representam um aumento de 12% e 16%, respetivamente.

O Algarve e a R.A. da Madeira registaram o crescimento mais elevado de alojamentos com 36% cada.

Edifícios e alojamentos, por NUTS II, variação 2001-2011

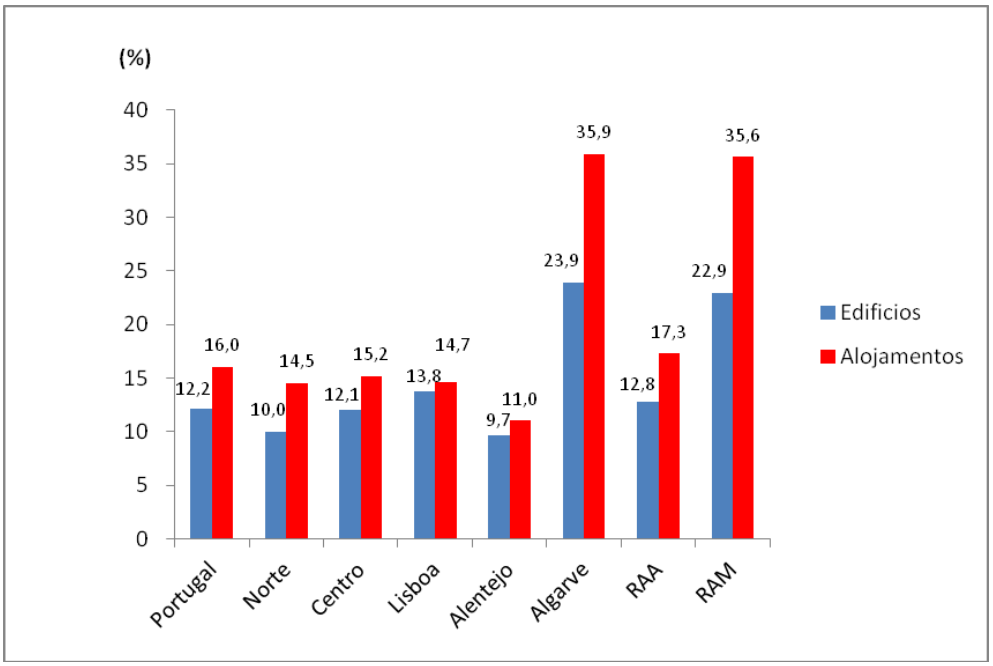

Alojamentos de residência secundária e vagos reforçam importância

Em 2011, os alojamentos clássicos distribuíam-se do seguinte modo: 3 991 112 residências habituais, 1 133 300 residências secundárias ou de uso sazonal e 735 128 vagos, representando respetivamente 68,2%, 19,3% e 12,5% do parque habitacional.

Distribuição da forma de ocupação dos alojamentos clássicos, por NUTS II, 2011

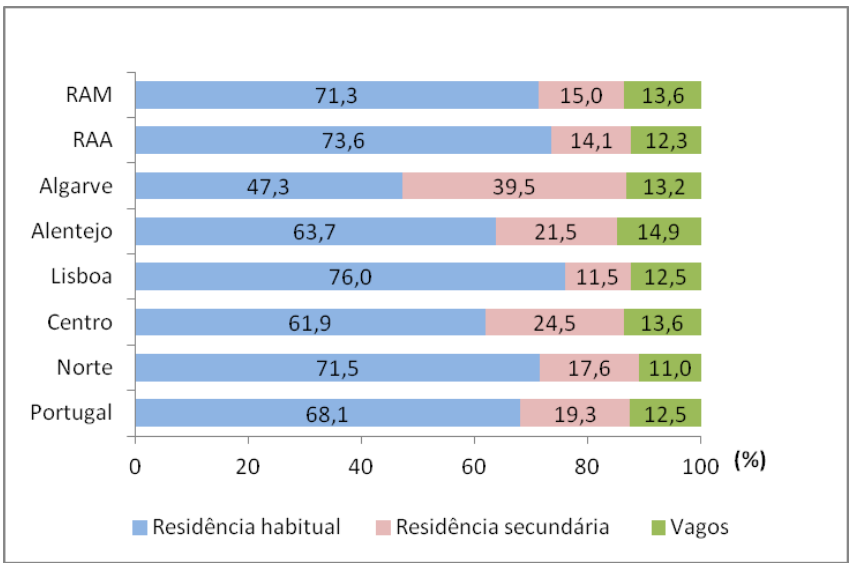

Lisboa detinha a maior percentagem de alojamentos de residência habitual (76%), a par da menor percentagem de residências secundárias (11,5%). No Algarve 40% do total dos alojamentos eram residências secundárias e 47,3% residência habitual.

Face a 2001, registou-se um acréscimo considerável nos alojamentos vagos (35,2%) e nos de residência secundária (22,6%), enquanto os alojamentos ocupados como residência habitual aumentaram 12,4%.

Aumenta o número de alojamentos com encargos por compra

A grande maioria (73%) dos alojamentos clássicos de residência habitual era ocupada pelo proprietário. Os alojamentos arrendados representam cerca de 20%, enquanto as restantes situações, como cedências ou empréstimos, significam apenas 6,8%.

Distribuição da condição de ocupação dos alojamentos, por NUTS II, 2011

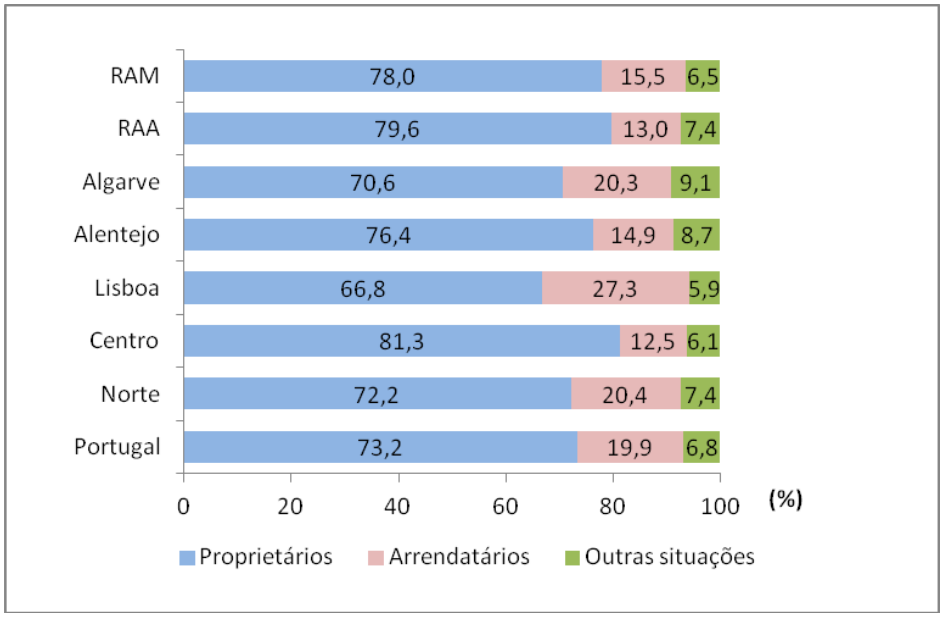

Lisboa era a região onde o arrendamento tem maior importância

No conjunto do País e face a 2001, o número de alojamentos arrendados aumentou 6,3%.

Lisboa era a região do país onde o número de casas arrendadas mais pesava (27%), seguindo-se as regiões do Norte e do Algarve, com cerca de 20% das residências em regime de arrendamento. A Região Centro era a que apresentava o valor mais baixo (12,9%).

Dos 2 923 271 alojamentos ocupados pelo proprietário em 57,1% não existiam encargos por aquisição da habitação. Os alojamentos em que existem encargos pela compra representavam 42,9%, mais 11 pp do que em 2001.

Distribuição dos proprietários com e sem encargos por compra, 2001 e 2011

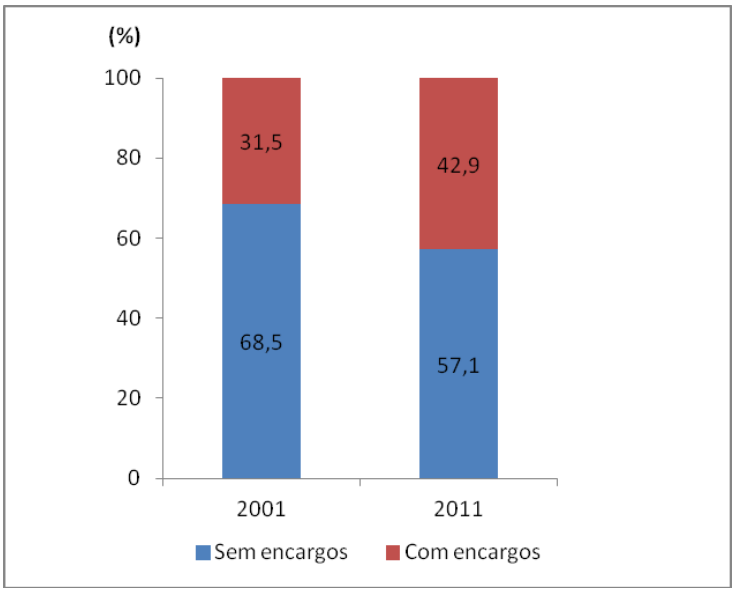

Mais de 50% dos alojamentos com encargos por compra, tinham encargos mensais entre os 250 e os 500 Euros, sendo que em 17,5% dos casos se situavam entre 400-499 Euros. Em 5,6% dos casos os encargos eram superiores a 800 Euros, peso idêntico ao dos alojamentos com encargos inferiores a 100 Euros.

Percentagem de proprietários segundo os escalões dos encargos por compra, 2011

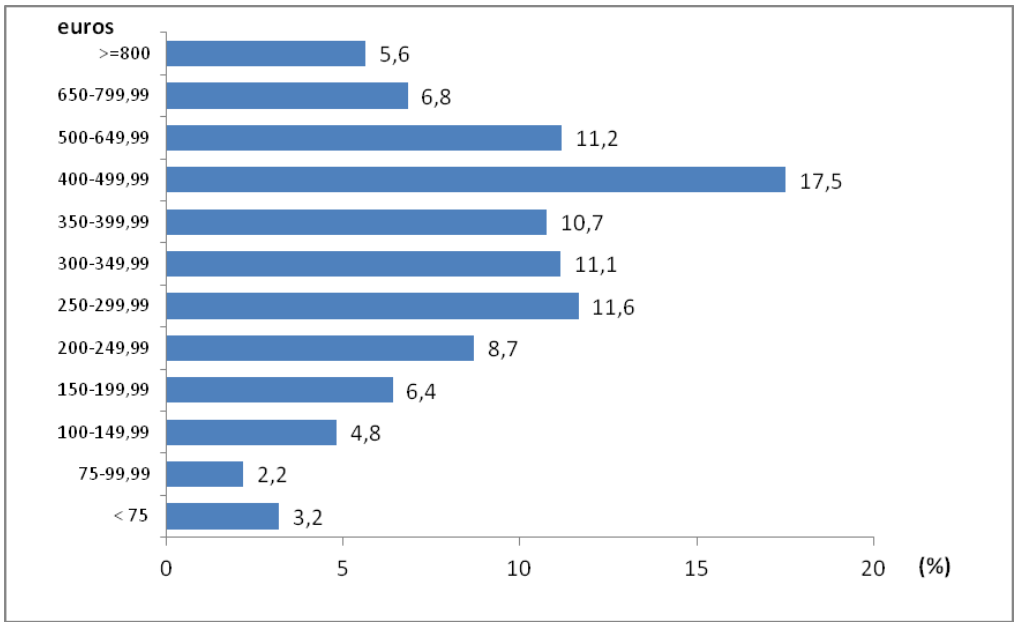

A maior parte dos alojamentos arrendados tinham contrato de duração indeterminada

No universo dos alojamentos arrendados, eram os portadores de contratos de arrendamento de duração indeterminada os que assumem a maior expressão 57,9%, seguindo-se os contratos com prazo certo (31,6%), de renda social ou apoiada (8,6%) e, por último, o subarrendamento, com uma expressão muito reduzida (2,0%).

As entidades proprietárias dos alojamentos arrendados eram, na sua larga maioria, particulares ou empresas privadas (81%), surgindo as autarquias locais com um peso bastante mais reduzido (10%). As restantes entidades proprietárias (ascendentes ou descendentes, Estado ou Institutos públicos e instituições sem fins lucrativos, Empresas públicas e cooperativas de habitação) não tinham grande expressão.

Mais de 36% dos arrendatários pagava uma renda situada entre 200 e 400 Euros e a cerca de 25% dos alojamentos correspondia uma renda mensal inferior a 75 Euros. As rendas situadas acima dos 650 Euros representavam apenas 3,4%.

Alojamentos arrendados, segundo o escalão do valor mensal da renda, 2011

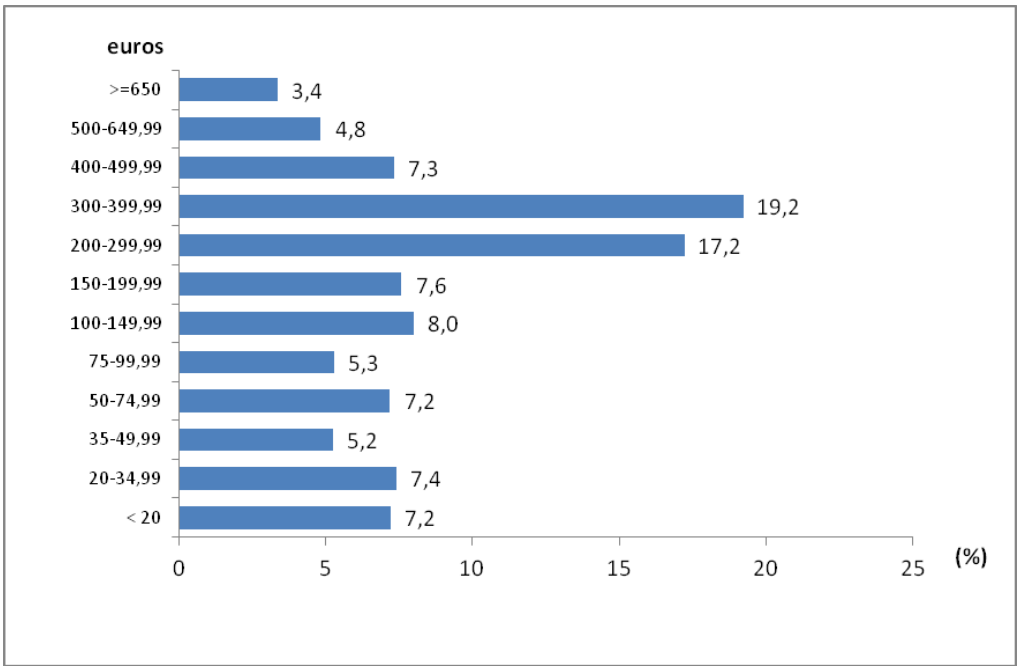

Valores dos encargos por compra superiores aos valores dos encargos com rendas

Os encargos por compra dos alojamentos atingiam, em 2011, um valor mensal médio de 395 Euros, representando um acréscimo de 35,7% nos últimos 10 anos.

Era nas Regiões Autónomas dos Açores e da Madeira que encargos médios mensais eram mais elevados, respetivamente 440 euros e 455 euros. Lisboa e Algarve, embora com valores mais baixos, apresentavam,

também, valores acima da média nacional, respetivamente 425 e 412 euros. Era no Alentejo, com 352 euros, que se observava o valor mais baixo. As regiões Norte e Centro apresentavam, igualmente, encargos médios abaixo da média do país, com 374 euros e 378 euros, respetivamente.

Valor médio mensal dos encargos por compra e das rendas, 2011

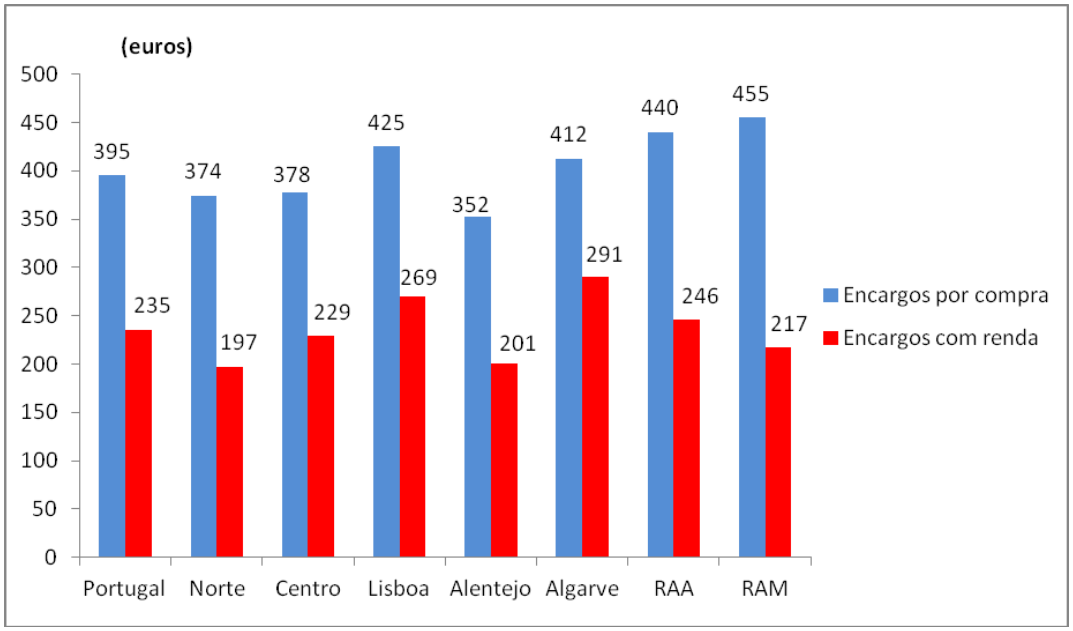

O valor médio mensal da renda de casa era de 235 euros, bastante mais baixo comparativamente ao valor do encargo mensal com a aquisição da habitação.

O valor das rendas de casa era mais elevado nas regiões de Lisboa e do Algarve, 269 e 291 euros, respetivamente, ocorrendo o mais baixo na Região Norte (197 euros). A Região Centro e a R.A da Madeira, com 229 e 217 euros, apresentam igualmente rendas inferiores à média nacional, assim como a Região do Alentejo, com 201 euros.

À semelhança do que se verificara na década de 90 e na década passada os encargos com aquisição de casa própria eram, em média, cerca de 70% mais elevados do que os encargos com rendas.

Lisboa era a região do país com os alojamentos mais pequenos

A área útil média dos alojamentos atingia cerca de 109 m^2, a que correspondia 4,98 divisões por alojamento.

Na Região de Lisboa os alojamentos eram, em média, de menor dimensão (96 m^2), enquanto que na R.A. dos Açores se localizavam os de maior dimensão, com 118 m^2 e 5,42 divisões por alojamento.

A maior parte dos alojamentos situava-se em edifícios unifamiliares

Os alojamentos destinados à habitação enquadravam-se, principalmente, em edifícios construídos para possuir 1 ou 2 alojamentos (57,8 %), enquanto os alojamentos em edifícios construídos para possuírem 3 ou mais alojamentos representam 41,5%, em termos nacionais. A média de alojamentos por edifício era de 1,6.

Alojamentos clássicos segundo o tipo de edifício, 2011

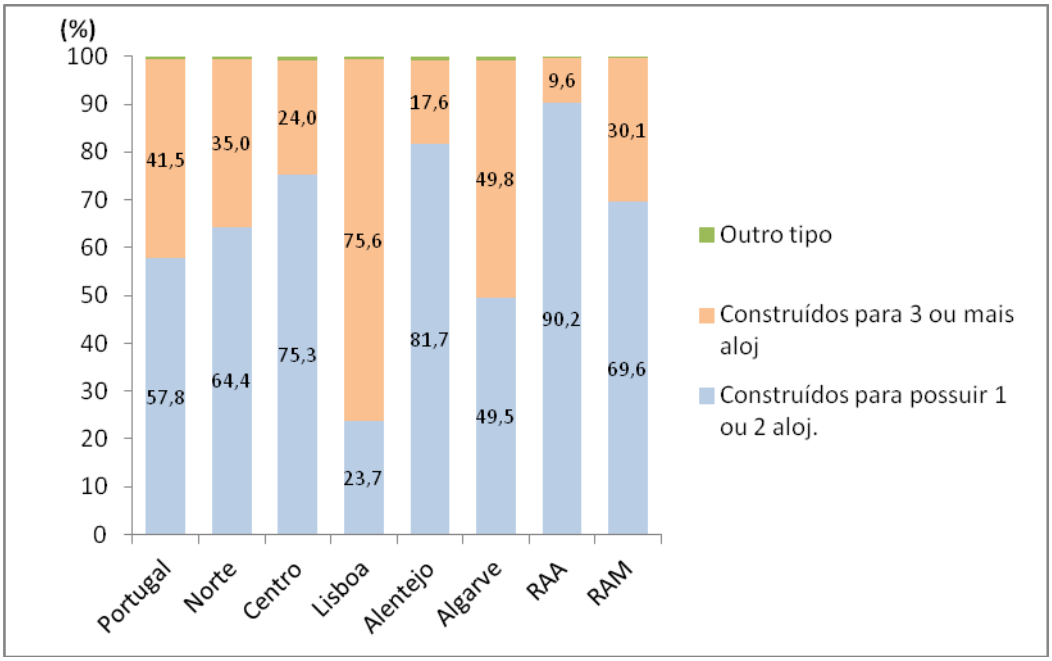

Verificavam-se grandes disparidades a nível regional:

Na Região de Lisboa, 75,6% dos edifícios foram estruturalmente construídos, para integrarem 3 ou mais alojamentos, proporção bastante superior à média nacional. Cada edifício tinha, em média, 3,3 alojamentos.

No extremo oposto, na R.A. dos Açores apenas 9,6% de alojamentos se situa em edifícios deste tipo, em média com 1,1 alojamentos.

A maioria dos edifícios habitacionais não necessitava de reparações

Os Censos 2011 reportam um parque habitacional pouco envelhecido, reflexo da dinâmica construtiva das últimas décadas, em que 71% dos edifícios se encontrava em bom estado de conservação, não necessitando de reparações, 27,2% necessitava de reparações e apenas 1,7% se encontrava muito degradado.

O índice de envelhecimento dos edifícios, apurado através dos Censos 2011, é de 176, o que significa que o número de edifícios construídos até 1960 é menos do dobro do que aqueles que foram construídos na última década (após 2001).

A Região do Alentejo distancia-se do padrão nacional, apresentando o parque habitacional mais envelhecido (291) e a percentagem mais elevada de edifícios degradados (2,1%).

A maioria dos edifícios não era acessível a pessoas com mobilidade condicionada

Cerca de 59% dos edifícios não tinham entrada acessível a pessoas com mobilidade condicionada e que se deslocam em cadeira de rodas. Esse acesso é possível em apenas 41% dos edifícios.

Nas regiões de Lisboa e Algarve os edifícios com acesso a cadeira de rodas, representavam cerca de 43%. A Região Norte e a R.A. da Madeira apresentavam o valor mais baixo, inferior a 40%.

Dentro dos edifícios o grau de acessibilidade era ainda menor, já que apenas 30% dos edifícios construídos para possuírem 3 ou mais alojamentos, dispunham de espaço comum interior para circulação em cadeira de rodas até à entrada do alojamento.

Inquérito de Qualidade

A operação Censos 2011 foi sujeita a um Inquérito de Qualidade, realizado de forma independente por entidade externa após a operação censitária, a fim de avaliarem eventuais erros de cobertura e de conteúdo da operação.

O Inquérito de Qualidade realizou-se junto de uma amostra de 63 mil edifícios e de 104 mil alojamentos. Foi ainda reinquirida uma amostra da população residente em 10 600 alojamentos.

Estima-se que se tenha registado uma sobrecobertura dos **edifícios** e dos **alojamentos** familiares recenseados em 2011 (+1,3% e +1,4%) respetivamente, devido essencialmente a classificação incorreta de alojamentos, decorrente da operacionalização de conceitos.

Ao nível do recenseamento das **famílias** e dos **indivíduos** residentes estima-se que se tenha registado uma subcobertura (-3,6% e -2,5%, respetivamente), decorrente das dificuldades de contato direto com a população, muito particularmente em meio urbano.

Estes indicadores demonstram que a qualidade dos resultados definitivos dos Censos 2011 está em linha com o registado em países com sistemas estatísticos desenvolvidos, designadamente o Canadá e o Reino Unido.